Fundamentos de Geoestatística

dr. Rachid Muleia, Msc. in Statistics

Universidade Eduardo Mondlane
Faculdade de Ciências
Departamento de Matemática e Informática

Fevereiro de 2019

Programa Temático

1. Introdução à Geoestatística
2. Abordagem probabilística e condições de estacionaridade
3. Análise exploratória de dados espaciais
4. Análise variográfica e estudo da anisotropia
5. Métodos de interpolação espacial

Avaliações

- A presença do estudante nas minhas aulas é de carácter "obrigatório". O estudante não deve ter mais que 25% de ausências.
- Ao longo do semestre faremos dois testes. A resolução das fichas práticas também é uma avaliação.
- Para além dos testes, iremos ter dois trabalhos práticos em grupo e dois trabalhos prático individuais. Por último, antes da data do exame, teremos um teste oral.

$$\text{Nota de Frequência} = 0.35 \times \text{TE I} + 0.35 \times \text{TE II} + 0.05 \times \text{Fichas} + 0.1 \times (\text{TPGI}+\text{TGII})/2 + 0.1 \times (\text{TPI}+\text{TPII})/2 + 0.05 \times \text{TO}$$

Ferramentas de análise

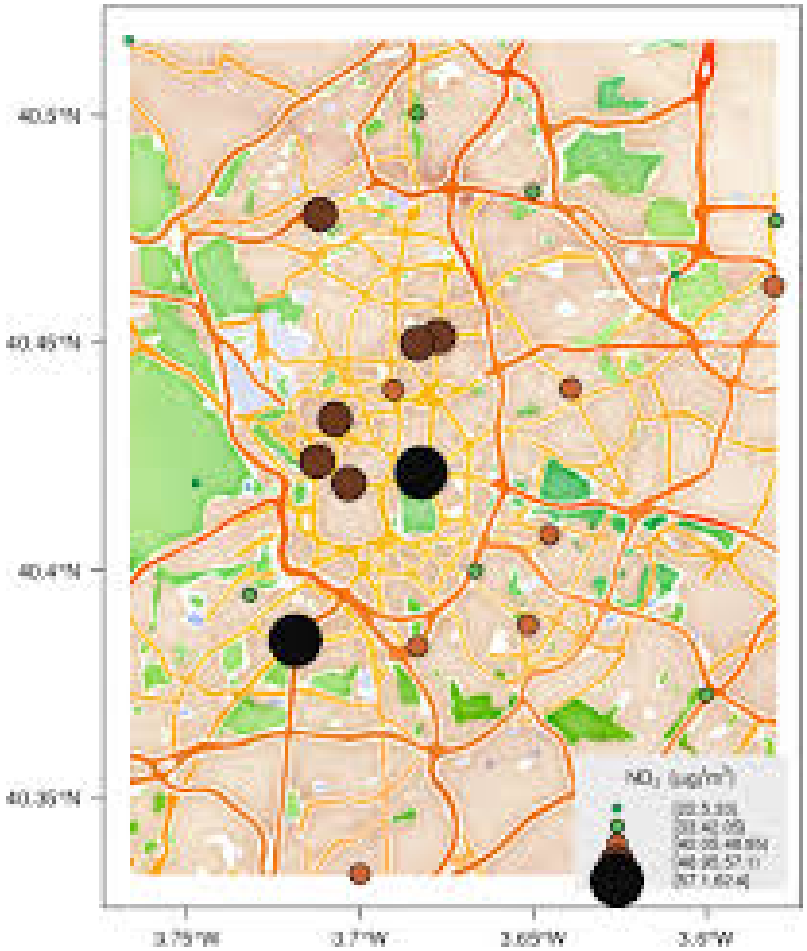

Porquê R??

- Software estatístico gratuito. É tambem uma linguangem de programação, e isto torna o prgrama flexível;
- Muito popular na comunidade académica. Actualmente conta com 2 milhões de usuários
- Encontra-se disponível na internet para downlaod em https://cran.r-project.org/bin/windows/base/
- Actualmente é acompanhado do Rstudio que, também, é grátis e pode ser baixado a partir da internet em https://www.rstudio.com/products/rstudio/download/

Referências recomendadas

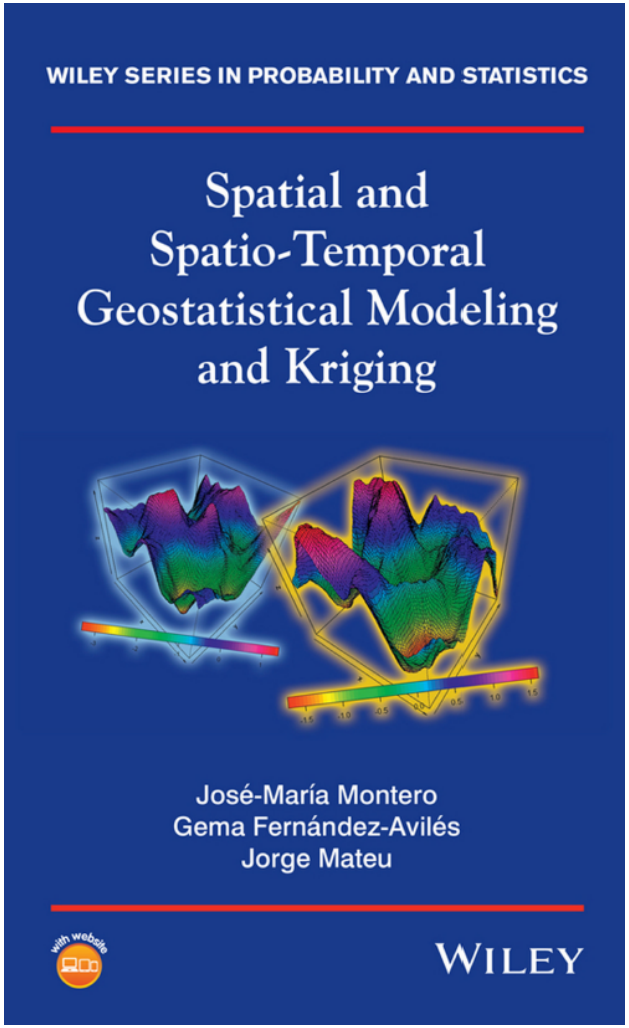



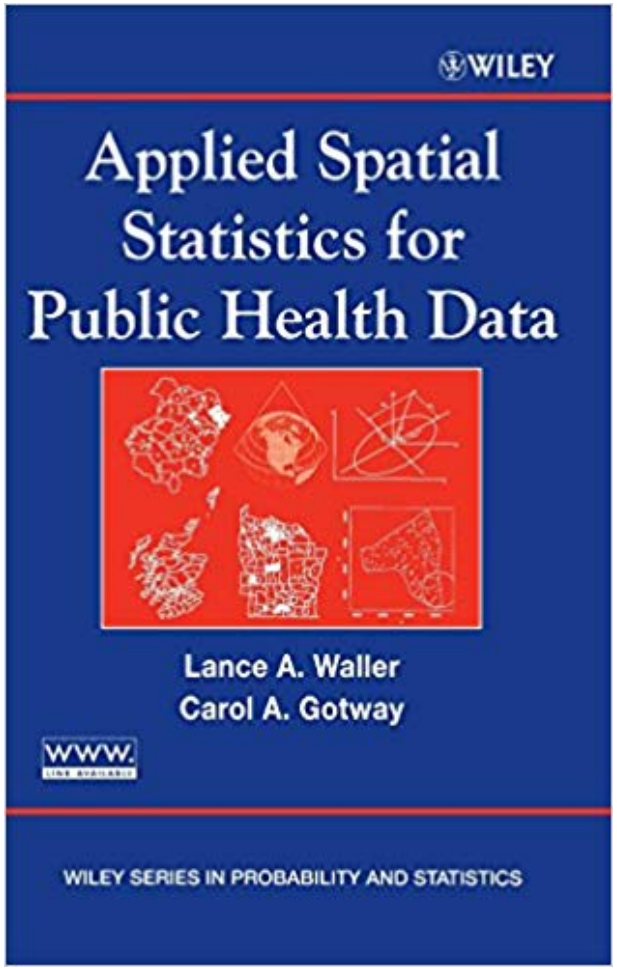

Introdução à Geoestatística

- Geo-estatística lida com a caracterização de dados espaciais e espacio-temporal;
- É uma ciência que surge da necessidade de modelação de recursos geológicos- caracterização espacial da concentração de metais em jazigos;
- Primeiros desenvolvimentos foram dados na África do Sul por D.G. Krige, um engenheiro de minas, e H.S. Sichel, um estaticista, por volta de 1950;
- Posteriormente, Georges Matheron, um engenheiro francês, expandiu o trabalho iniciado por D.G. Krige, dando origem a modelos de krigagem;

Porquê geo-estatística

- Maior parte dos fenómenos/grandezas variam ao longo do espaço, e a geo-estatística ajuda a perceber e quantificar a variabilidade espacial de um dado fenómeno;
- Estatística clássica assume independência das observações, enquanto que dados geo-referenciados apresentam dependência espacial;
- Observações mais próximas apresentam maior dependência espacial, e as mais afastadas apresentam menor dependência espacial;
- Ignorar a depedência espacial pode condicionar a validade das análises estatística.

Processo espacial-Definições básicas

Variável regionalizada:

$\rightarrow$ Toda variável distribuída no espaço é tida como "regionalizada" ou "espacial". Por example:

1. Concentração de fósforo nas machambas do vale do infulene.
2. Níveis de precipitação na cidade de Maputo.

$\rightarrow$ Uma variável regionalizada pode ser vista como, uma função $f(\boldsymbol{s})$, que assume um dado valor em cada ponto $\boldsymbol{s}$, num espaço propriamente definido.

Função aleatória

$\rightarrow$ Seja $Z(\boldsymbol{s}_i)$ o valor observado de uma variável de interesse em uma posição $\boldsymbol{s}_i$. Este valor pode ser tido como uma realização particular de uma variável aleatória $Z(\boldsymbol{s}_i)$ em um ponto $\boldsymbol{s}_i$.

$\rightarrow$ O conjunto de variáveis aleatórias $\{Z(\boldsymbol{s}) : \boldsymbol{s} \in R\}$, onde R é uma região de interesse(ex: campo de plantação), é tido como uma função aleatória. Por exemplo: $\{Z(\boldsymbol{s}) : \boldsymbol{s} \in R\}$, onde:

- $Z(\boldsymbol{s}) =$ valor observado no ponto $\boldsymbol{s} = (x_1, x_2)$ ou $\boldsymbol{s} = (x_1, x_2, x_3)$
- $R =$Conjunto de todos pontos sobre a área de interesse

Tipos de dados

Seja $\boldsymbol{s} \in R$ uma localização genérica num espaço euclidiano de dimensão d e seja $\{Z(\boldsymbol{s}) : \boldsymbol{s} \in R\}$ função aleatória espacial, em que Z denota o atributo de interesse.

Dados geo-estatísticos (dados de superfície)

Dados geo-estatísticos surgem quando o domínio em estudo é um conjunto fixo e contínuo:

- $Z(\boldsymbol{s})$ pode ser observado em qualquer ponto do domíno D;
- O domínio D é não-estocástico;

Dados de área/regionais (lattice data)

Os dados de área surgem, quando o domínio/região em estudo é de natureza discreta, e $Z(\boldsymbol{s})$ pode ser observado em locais fixos que possam ser devidamente enumerados. Os locais podem ser: Províncias, distritos, regiões. Para este tipo de dados, os dados, normalmente, aparecem de forma agregada.

Dados de ponto padrão

Diferentemente dos dados geoestatísticos e regionais, nos dados de ponto padrão a região de interesse não é fixa, mas sim aleatória. Este tipo de dado surge quando o interesse reside em estudar/analisar os locais onde os eventos de interesse ocorrem.

Estacionariedade

→ Em geo-estatística o processo inferencial depende da estacionariedade da variável regionalizada.

→ Pode-se pensar da estacionariedade como sinónimo de homogeniedade da variável regionalizada na região em estudo.

→ Assume-se a estiocionariedade, pois a variável regionalizada só pode uma assumir uma única realização(isto contradiz o conceito de uma variável aleatória).

→ Comportamento regular dos momentos de uma função aleatória sobre uma região ou intervalo de tempo.

Estacionariedade estrita:

$\rightarrow$ Uma função aleatória é estacionária de forma estrita, se a família de v.a's $Z(\boldsymbol{s}_1), Z(\boldsymbol{s}_2), \ldots, Z(\boldsymbol{s}_k)$ e $Z(\boldsymbol{s_1} + \boldsymbol{h}), Z(\boldsymbol{s_2} + \boldsymbol{h}), \ldots, Z(\boldsymbol{s_k} + \boldsymbol{h})$ para $\forall\ k$ e $\boldsymbol{h}$ a distribuição conjunta de probablidades é a mesma.

$\rightarrow$ A distribuição de conjunta de probabilidades de $\{Z(\boldsymbol{s}_1), Z(\boldsymbol{s}_2), \ldots, Z(\boldsymbol{s}_k)\}$ não depende de qualquer que seja a translação de $\boldsymbol{h}$.

$\rightarrow$ A hipótese de estacionariedade estrista é bastante rigorosa, podendo se relaxar usando a hipótese de estacionariedade de segunda ordem.

Exemplo de estacionariedade estrita

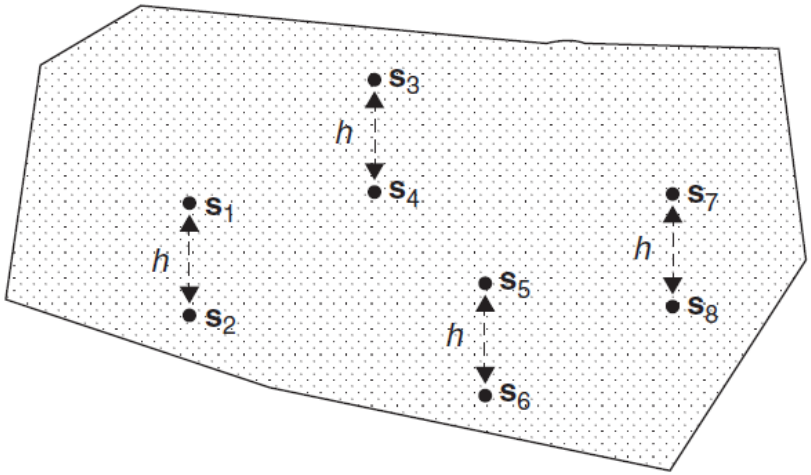

Figure 1: Quatro pares de pontos separados por uma distância h

No caso de estacionariedade estrita $\{Z(\boldsymbol{s}_1), Z(\boldsymbol{s}_2)\}$, $\{Z(\boldsymbol{s}_3), Z(\boldsymbol{s}_4)\}$ e $\{Z(\boldsymbol{s}_5), Z(\boldsymbol{s}_6)\}$ têm a mesma distribuição bivariada de probabilidades, pois a distância entre os pares $\{\boldsymbol{s}_1, \boldsymbol{s}_2\}$, $\{\boldsymbol{s}_3, \boldsymbol{s}_4\}$ e $\{\boldsymbol{s}_5, \boldsymbol{s}_6\}$ é a mesma.

Estacionariedade de segunda ordem:

$\rightarrow$ A hipótese de estacionariedade de segunda ordem exige apenas que os dois primeiros momentos da função aleatória estejam definidos.

- $E(Z(\boldsymbol{s})) < \infty$ e $E((Z(\boldsymbol{s})) = \mu(\boldsymbol{s}) = \mu$, e não de pende da posição $\boldsymbol{s}$:
- $C(Z(\boldsymbol{s}), Z(\boldsymbol{s}+\boldsymbol{h})) < \infty$,
- $C(Z(\boldsymbol{s}), Z(\boldsymbol{s}+\boldsymbol{h})) = C(\boldsymbol{h}), \forall \boldsymbol{s} \in R \quad \text{and} \quad \boldsymbol{h}$

$\rightarrow$ A estacionariedade de segunda ordem pode ser interpretada como se a variável regionalizada assumisse valores que flutuam em volta de um valor constante (média), e a variação dessas flutuações fosse a mesma em todo o domínio.

- Se a covariância existe, e é finitia, então a variância está definida, e por sua vez é constance $V(Z(\boldsymbol{s})) = C(\mathbf{0})$,

- No caso de estacionariedade de segunda ordem, a covariância e o semivariograma são equivalentes:

$$
\begin{aligned}
\gamma(\boldsymbol{h}) &= \frac{1}{2}\mathsf{Var}\{Z(\boldsymbol{s}+\boldsymbol{h}) - Z(\boldsymbol{s})\} \\
&= \frac{1}{2}\Big\{\mathsf{Var}[Z(\boldsymbol{s}+\boldsymbol{h})] + \mathsf{Var}[Z(\boldsymbol{s})] - 2C[Z(\boldsymbol{s}+\boldsymbol{h}), Z(\boldsymbol{s})]\Big\} \\
&= \frac{1}{2}C(\mathbf{0}) + \frac{1}{2}C(\mathbf{0}) - \frac{2}{2}C(\boldsymbol{h}) \\
&= C(\mathbf{0}) - C(\boldsymbol{h})
\end{aligned}
$$

Estacionariedade de intrínseca:

$\rightarrow$ Uma função aleatória é instrinsecamente estacionária, se para qualquer translação $\boldsymbol{h}$, as primeiras diferenças $Z(\boldsymbol{s}+\boldsymbol{h}) - Z(\boldsymbol{s})$ são estacionárias de segunda ordem.

- $E\big(Z(\boldsymbol{s}+\boldsymbol{h}) - Z(\boldsymbol{s})\big) = 0$
- $V\big(Z(\boldsymbol{s}+\boldsymbol{h}) - Z(\boldsymbol{s})\big) = 2\gamma(\boldsymbol{s})$

$\rightarrow$ A grandeza $2\gamma(\boldsymbol{s})$ é conhecida como variograma, e é um parâmetro de extrema importância em geo-estatística.

Variograma/Semivariograma

$\rightarrow$ O objectivo primordial da geo-estatística é a previsão (Krigagem/interpolação espacial) do fenómeno em estudo em lugares não amostrados;

$\rightarrow$ A interpolção espacial depende da análise variográfica;

$\rightarrow$ O semivariograma é dados por :

$$\gamma(\boldsymbol{h}) = \frac{1}{2}V\big(Z(\boldsymbol{s}_i) - Z(\boldsymbol{s}_j)\big), \forall \boldsymbol{s}_i, \boldsymbol{s}_j \in R$$

$\rightarrow$ O variograma é usado para descrever a dependência espacial da variável regionalizada.

$\rightarrow$ Se o preocesso for estacionário de segunda ordem e instriscecamente estacionário, então:

$$\gamma(\boldsymbol{h}) = \frac{1}{2}V(Z(\boldsymbol{s}+\boldsymbol{h}) - Z(\boldsymbol{s}) = \frac{1}{2}E((Z(\boldsymbol{s}+\boldsymbol{h}) - Z(\boldsymbol{s}))^2),$$

mostra como a dissimilaridade entre $Z(\boldsymbol{s}+\boldsymbol{h})$ e $Z(\boldsymbol{s})$ aumenta com a distância $\boldsymbol{h}$.

$\rightarrow$ O semivariograma que depende apenas da distância de separação das observações, e não da direção, é tido como isotrópico. Se este, por sua vez, for intrinsecamente estacionário, o processo é tido como homogênio.

Semivariograma experimental

$\rightarrow$ Na prática usa-se o semivariograma experimental para estudar a dependência espacial dos dados;

$\rightarrow$ Usa os dados observados da variável regionalizada para estimar variabilidade espacial do fenómeno em estudo;

$\rightarrow$ O estimador do semivariograma é dado por:

$$\hat{\gamma}(\boldsymbol{h}) = \frac{1}{2\#N(\boldsymbol{h})} \sum_{N(\boldsymbol{h})} (Z(\boldsymbol{s}_i + \boldsymbol{h}) - Z(\boldsymbol{s}_i))^2,$$

e é designado por estimador clássico. $\#N(\boldsymbol{h})$ representa o número de pares de observações que são separados por uma distância $\boldsymbol{h}$;

$\rightarrow$ A representação gráfica de $\hat{\gamma}(\boldsymbol{h})$ versus $|\boldsymbol{h}|$ é designada por semivariograma experimental;

$\rightarrow$ O estimador do semivariograma $\hat{\gamma}(\boldsymbol{h})$ é um estimador não enviesado:

$$E(\hat{\gamma}(\boldsymbol{h})) = E\Big(\frac{1}{2\#N(\boldsymbol{h})}\sum_{N(\boldsymbol{h})}(Z(\boldsymbol{s}_i+\boldsymbol{h})-Z(\boldsymbol{s}_i))^2\Big) = \gamma(\boldsymbol{h})$$

Geralmente, na prática, o semivariograma é calculado para distâncias inferiores a metade do diametro do domínio de estudo. Isto porque, o número de pares diminue com a distância, e para distâncias maiores, o número de pares não é suficiente para produzir estimativas credíveis.

```r
path='C:/Users/lucp8943/Dropbox/Geostatistics Class Material/Lecture notes'
hiv.df_prop=read.csv(paste(path, 'hiv_prev.csv', sep='/'), header=TRUE); head(hiv.df_prop)
```

```
##         lat     long      prev
## 1 -15.27855 32.12809  0.000000
## 2 -25.95078 32.33560 25.000000
## 3 -25.83233 32.34203 13.888889
## 4 -25.34178 32.35649 14.893617
## 5 -25.94245 32.44658  8.620690
## 6 -25.82849 32.45118  6.976744
```

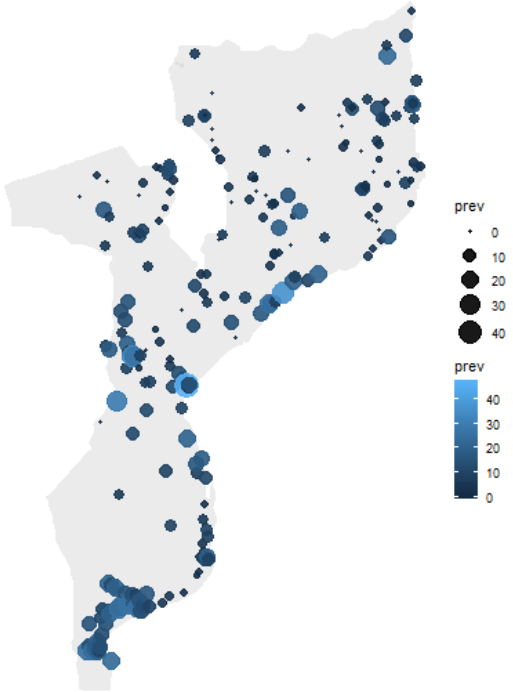

Figure 2: Prevalência de HIV/SIDA por área de enumeração (AE)

```r
##install.packages('geoR') # primeiro instalar o pacote geoR
suppressMessages({library('geoR')}) # chamar o pacote geoR
hiv_geo=as.geodata(hiv.df_prop, coords.col = c(2,1),data.col = 3)
summary(hiv_geo)
```

```
## Number of data points: 270
##
## Coordinates summary
##         long       lat
## min 32.12809 -26.16241
## max 40.69896 -10.73105
##
## Distance summary
##          min          max
## 6.596969e-04 1.726818e+01
##
## Data summary
##      Min.   1st Qu.    Median      Mean   3rd Qu.      Max.
##  0.000000  2.797619  7.643622  8.864440 13.043478 46.511628
```

```r
variograma=variog(hiv_geo, max.dist=15)
plot(variograma)
```

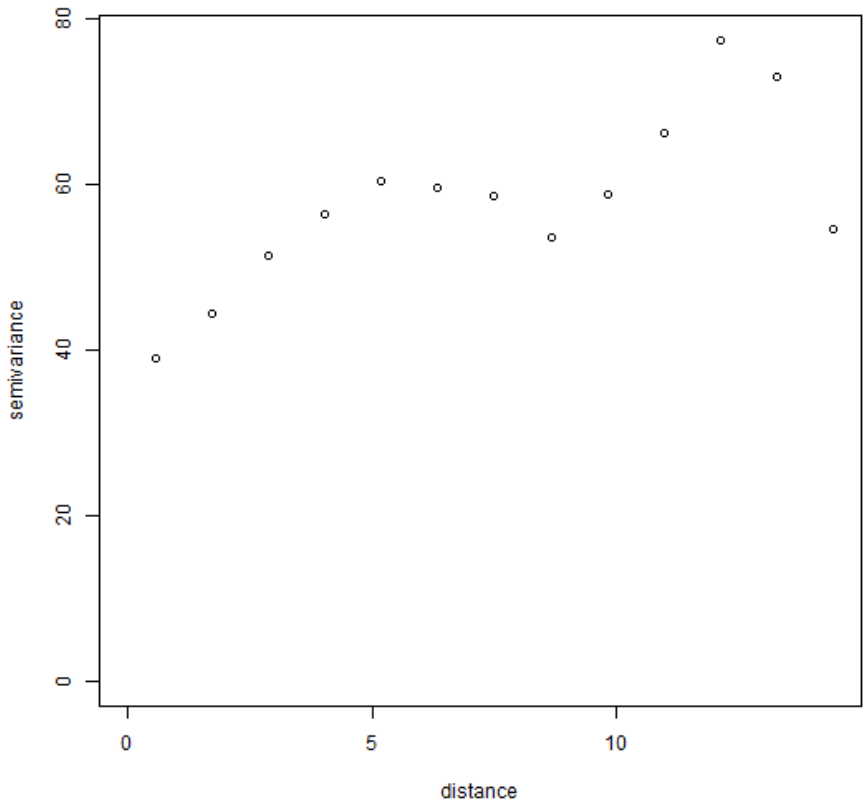

Estimação robusta do semivariograma

O estimador clássico do semivariograma apresenta algumas desvantagens:

- Extremamente sensível a valores atípicos;
- $(Z(\boldsymbol{s}+\boldsymbol{h})-Z(\boldsymbol{s}))^2 \sim 2\gamma(\boldsymbol{h})\chi_1^2$, consequentemente, $2\gamma(\boldsymbol{h})$ tem uma distribuição bastante assimétrica;

Como forma de remediar, Cressie and Hawkins (1980) propuseram :

$$2\bar{\gamma}(\boldsymbol{h}) = \frac{1}{0.457+0.494/N(\boldsymbol{h})}\left\{\frac{1}{N(\boldsymbol{h})}\sum_{i=1}^{N(\boldsymbol{h})}\left[|Z(x_i+\boldsymbol{h})-Z(x_i)|\right]^{1/2}\right\}^4$$

Exemplo-DATA BREAK: Dados de pH da Smoky Mountain

- O pH nas águas do riacho pode afectar os organismos do riacho
- Mudança do pH pode ser um indicador de poluição
- $0 <$ pH < 14, pH $<$ 7-ácido, pH $>$ 7-alcalino

	northing	easting	ph	elevation
1	-79.19	-22.53	7.91	0.244
2	-61.66	-55.39	7.14	0.375
3	-69.63	-31.93	6.81	0.567
4	-54.82	-44.38	6.97	0.512
5	-62.14	-37.94	7.21	0.408
6	-55.29	-14.60	6.94	0.512
7	-62.27	-23.30	6.59	0.506
8	-55.78	-13.17	6.94	0.488
9	-54.48	-28.70	6.94	0.488
10	-65.00	-6.62	8.43	0.232

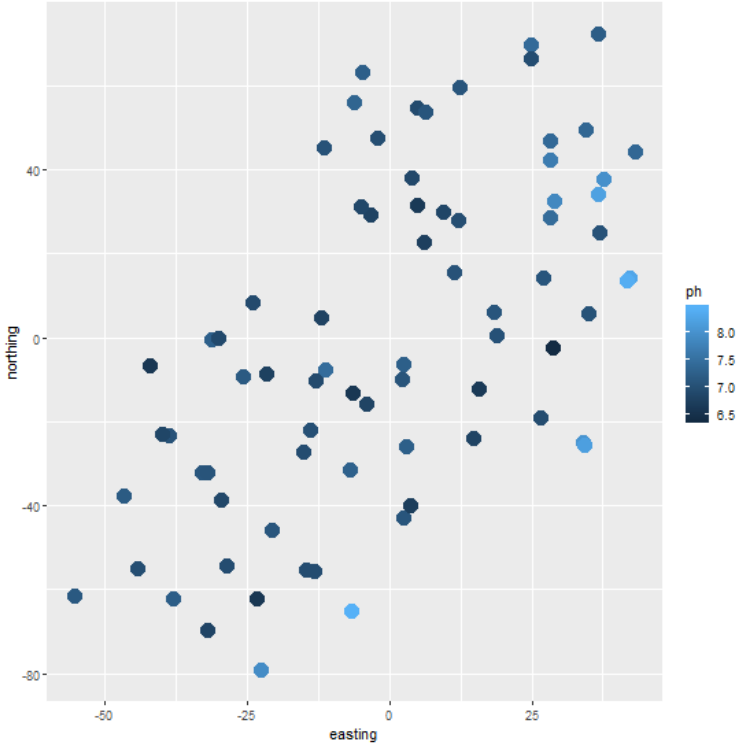

```r
path='C:/Users/lucp8943/Dropbox/Geostatistics Class Material/Lecture notes'
ph_df=read.table(paste(path, 'ph_data.txt',sep='/'),sep="",header=TRUE)
ph_geo=as.geodata(ph_df,coords.col=c(2,1),data.col=3)
variogram_ph=variog(ph_geo,max.dis=120)
```

```
## variog: computing omnidirectional variogram
```

```r
variogram_ph
```

```
## $u
##  [1]   4.614145  13.842436  23.070726  32.299017  41.527308  50.755598
##  [7]  59.983889  69.212179  78.440470  87.668760  96.897051 106.125341
## [13] 115.353632
##
## $v
##  [1] 0.0579369 0.1201206 0.1594079 0.1737550 0.1626211 0.2152035 0.2005385
##  [8] 0.2732983 0.1865881 0.2541853 0.2295052 0.1987260 0.2042285
##
## $n
##  [1]  42 189 258 339 311 288 286 258 193 174 134  98  79
##
## $sd
##  [1] 0.1185887 0.2396956 0.3161247 0.2687749 0.3072735 0.3543915 0.3181760
##  [8] 0.3716392 0.2824465 0.3649581 0.3585341 0.2872941 0.3110783
##
## $bins.lim
##  [1] 1.000000e-12 9.228291e+00 1.845658e+01 2.768487e+01 3.691316e+01
##  [6] 4.614145e+01 5.536974e+01 6.459803e+01 7.382632e+01 8.305462e+01
## [11] 9.228291e+01 1.015112e+02 1.107395e+02 1.199678e+02
##
## $ind.bin
##  [1] TRUE TRUE TRUE TRUE TRUE TRUE TRUE TRUE TRUE TRUE TRUE TRUE TRUE
##
## $var.mark
## [1] 0.1930417
##
```

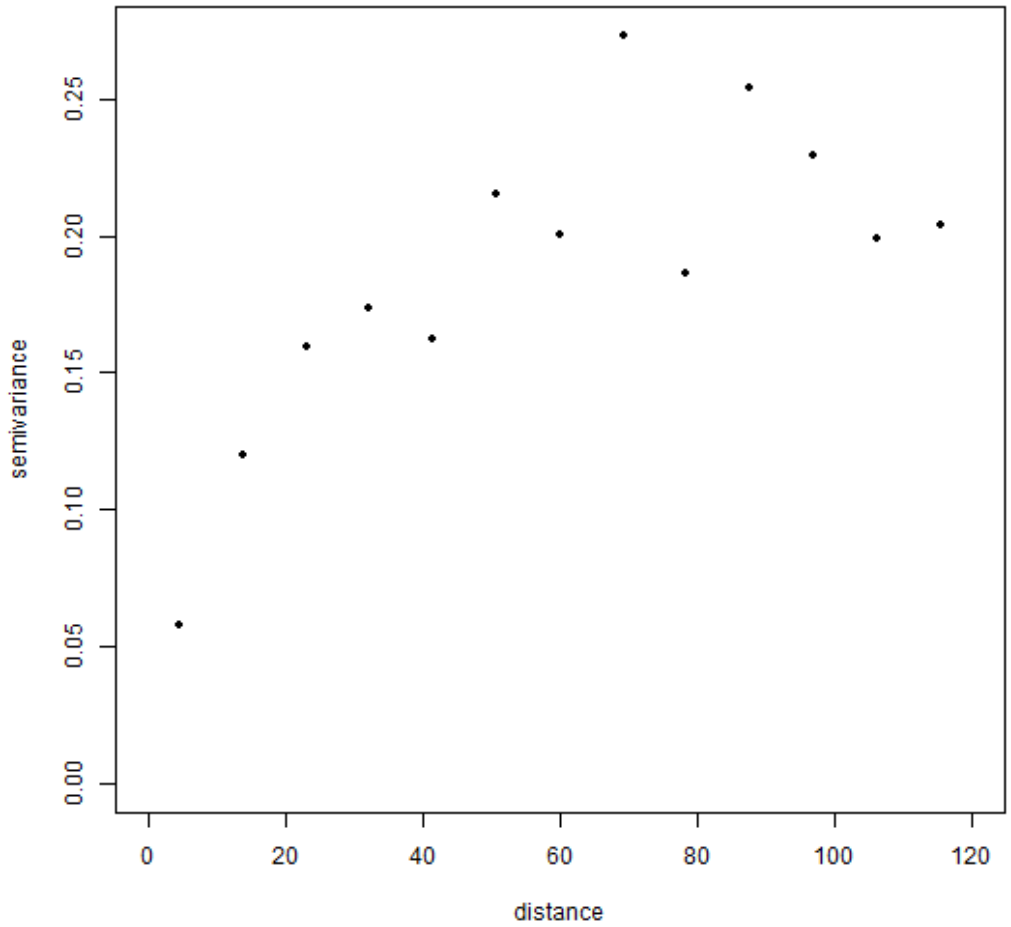

Figure 4: Semivariograma empirico para os valores do pH

Características do semivariograma

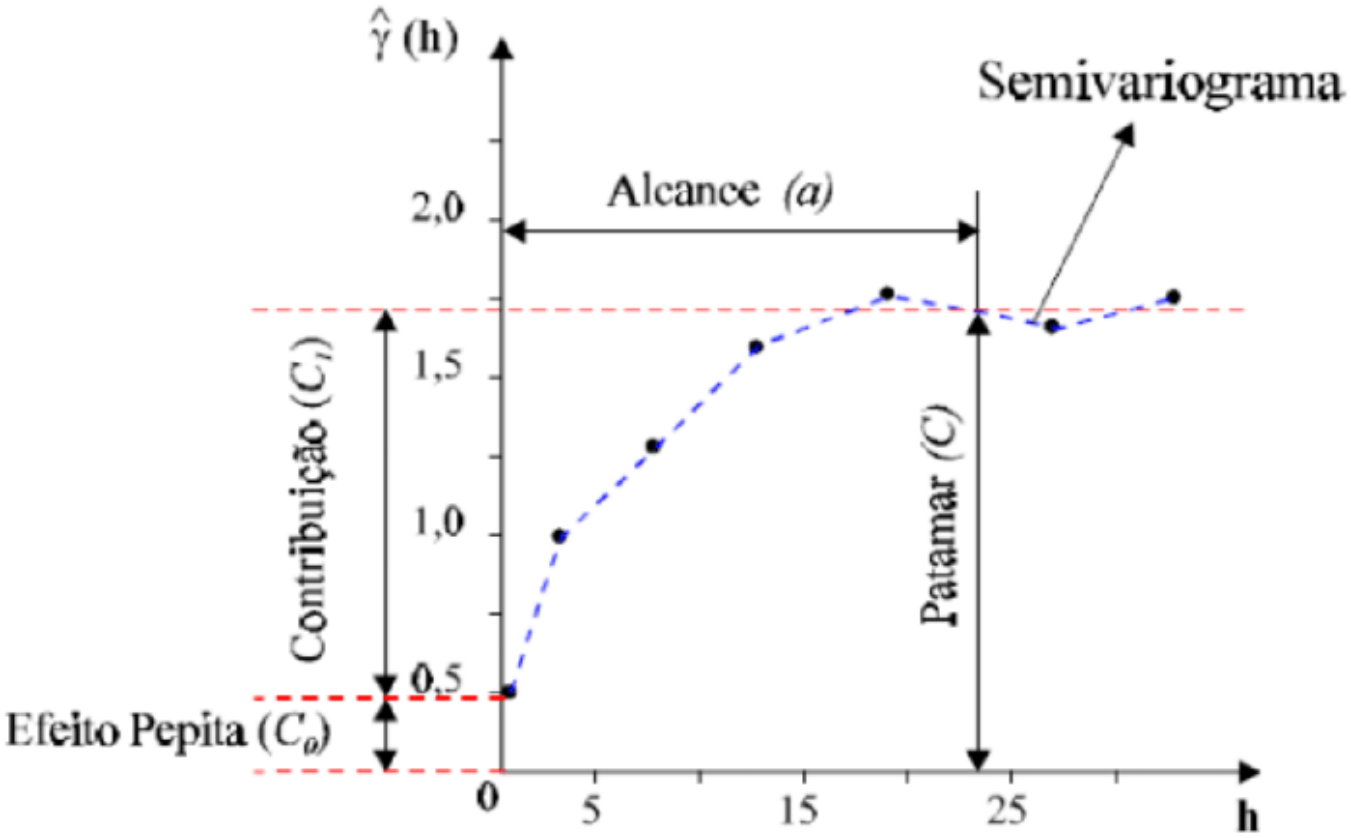

Figure 5: Parâmetros do semivariograma.

Efeito pepita- Valor do semivariograma para $\boldsymbol{h} = 0$. Representa micro variações devido a erros de medição.

Amplitude- Distância em que o variograma atinge o patamar, ou por outra, distância a partir da qual os dados não estão correlacionados.

Patamar/soleira-Valor do semivariograma para uma distância igual a amplitude.

Ajustamento do modelo de semivariogram

$\rightarrow$ O processo de interpolação espacial por meio de Krigagem depende da escolha de um modelo teórico de semivariograma.

$\rightarrow$ O modelo teórico de semivariograma deve cumprir algumas condições

- $\gamma(\boldsymbol{h}) = \gamma(-\boldsymbol{h})$
- $\gamma(\mathbf{0}) = 0$, visto que, $V(Z(\boldsymbol{s}) - Z(\boldsymbol{s})) = 0$
- $\gamma(\cdot)$ deve ser negativa definida, isto é,

$$\sum_{i=1}^{m}\sum_{j=1}^{m} a_i a_j \gamma(\boldsymbol{s}_i - \boldsymbol{s}_j) \leq 0$$

- O modelo deve ser isotrópico, isto é, o semivariograma depende apenas da distância de separação entre as observações.

$\rightarrow$ Para além das proprieadades acima mencionadas, é preciso encontrar um modelo que que tenha uma curvatura similar a do variograma empírico.

$\rightarrow$ O semivariograma experimental não pode ser usado, pois, não cumpre com as condições acima descritas de um modelo de semivariograma teórico.

$\rightarrow$ Existem vários modelos de semivariogramas. Para esta disciplina, vamo-nos limitar nos modelos paramétricos (modelos com uma expressão matemática analiticamente definida).

Modelo esférico

$$\gamma(\boldsymbol{h}, \boldsymbol{\theta}) = \begin{cases} 0, & h = 0 \\ c_0 + c_s\left[1.5(h/a_s) - 0.5(h/a_s)^3\right], & 0 < h < a_s \\ c_0 + c_s, & h \geq a_s \end{cases}$$

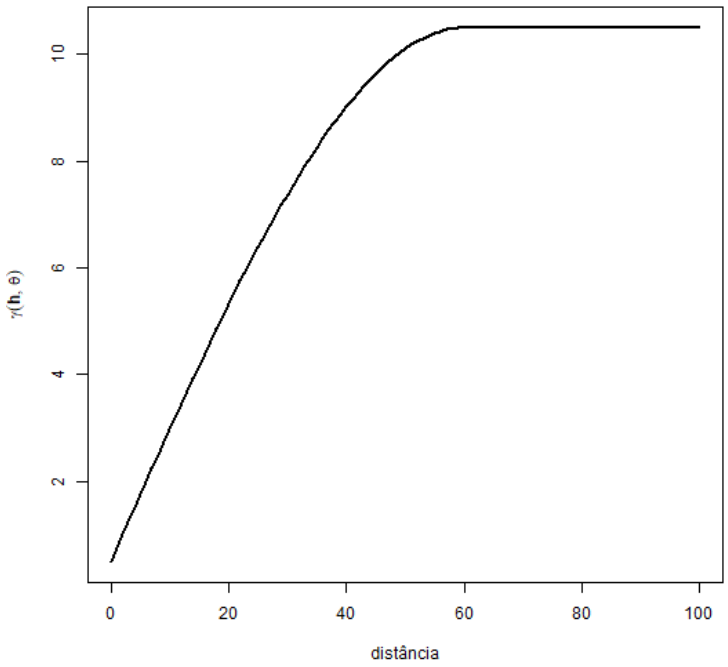

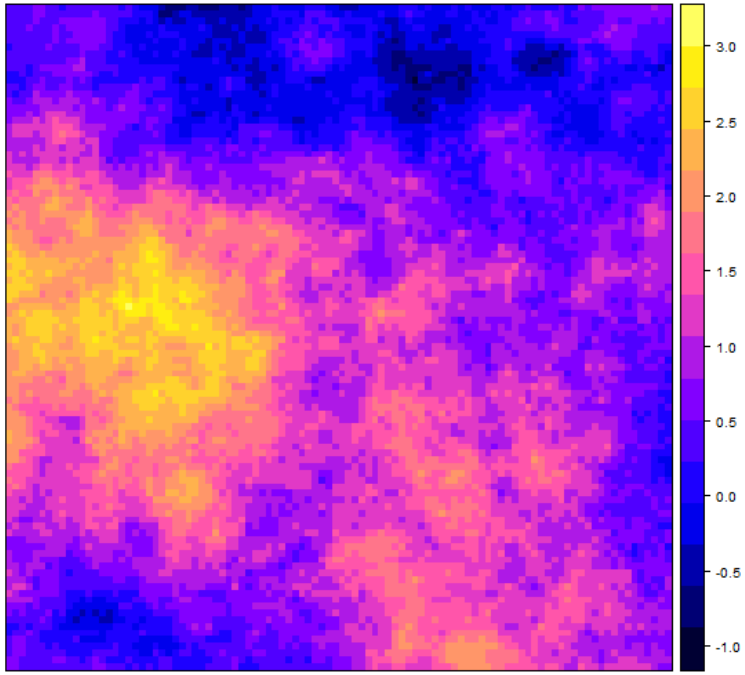

Modelo exponencial

$$\gamma(\boldsymbol{h}, \boldsymbol{\theta}) = \begin{cases} 0, & h = 0 \\ c_0 + c_e[1 - \exp(-h/a_e)], & h > a_e \end{cases}$$

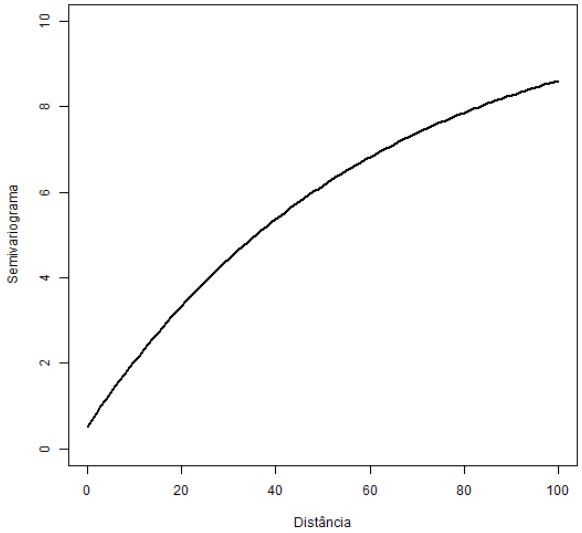

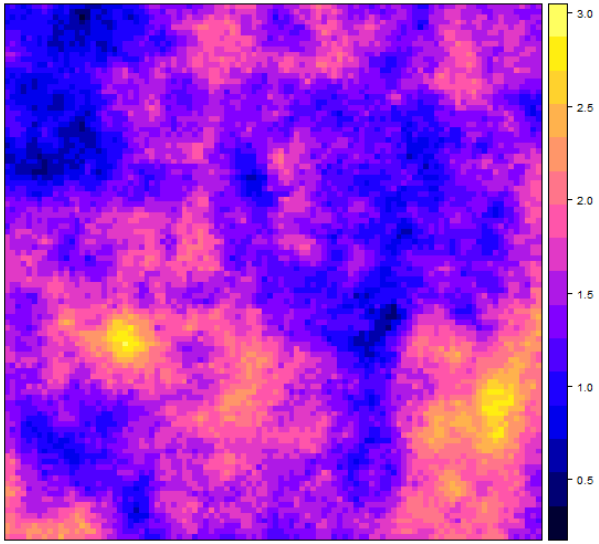

- A soleira é alcançada assimptopticamente quando $|\boldsymbol{h}| \to \infty$
- Amplitude prática/efectiva $a' = 3a$ corresponde a distância na qual o valor do semivariogram é 95% da soleira

Modelo Gaussiano

$$\gamma(\boldsymbol{h}, \boldsymbol{\theta}) = \begin{cases} 0, & h = 0 \\ c_0 + c_g[1 - \exp((-h/a_g)^2)], & h > a_g \end{cases}$$

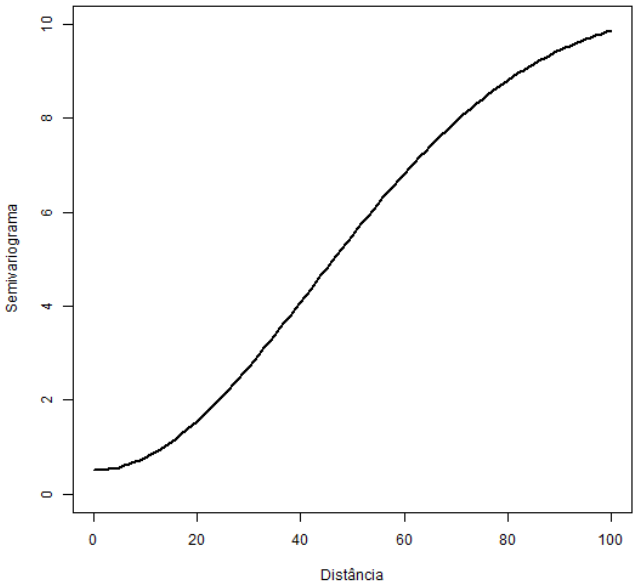

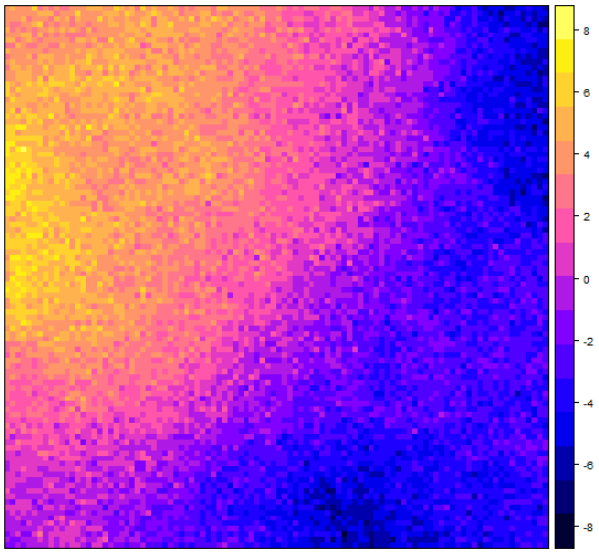

- A soleira também é alcançada assimptopticamente
- Calcule a amplitude efectiva para o modelo Gaussiano (Exercício)

$\rightarrow$ Mínimos quadrados ordinários- A estimação é feita minimizando a seguinte expressão:

$$\min \sum_{h} \left(\gamma(\boldsymbol{h}) - \hat{\gamma}(\boldsymbol{h})\right)^2$$

$\rightarrow$ Mínimos quadrados ponderados-Os quadrados dos resíduos são atribuídos um ponderador.

- Pode se usar número de pontos que distam h, isto é, $N(\boldsymbol{h})$

$$\min \sum_{h} N(\boldsymbol{h})\left(\gamma(\boldsymbol{h}) - \hat{\gamma}(\boldsymbol{h})\right)^2$$

- MQP de Cressie tem como ponderador $\dfrac{N(\boldsymbol{h})}{\gamma(\boldsymbol{h})^2}$, logo, a estimação é feita usando:

$$\min \sum_{h} N(\boldsymbol{h})\Big(\frac{\hat{\gamma}(\boldsymbol{h})}{\gamma(\boldsymbol{h})} - 1\Big)^2$$

Exemplo

```
ph_geo=as.geodata(ph_df,coords.col=c(2,1),data.col=3)
variogram_ph=variog(ph_geo,uvec = seq(0,120,l=10),messages = FALSE)
fit1=variofit(variogram_ph,cov.model="sph",ini.cov.pars=c(0.23,60),
             fix.nugget=FALSE,nugget=0,weights='equal',messages=FALSE)
fit2=variofit(variogram_ph,cov.model="exponential",ini.cov.pars=c(0.23,60),
             fix.nugget=FALSE,nugget=0,weights='equal',messages=FALSE)
fit1
```

```
## variofit: model parameters estimated by OLS (ordinary least squares):
## covariance model is: spherical
## parameter estimates:
##   tausq sigmasq     phi
##  0.0434  0.1786 60.3042
## Practical Range with cor=0.05 for asymptotic range: 60.30417
##
## variofit: minimised sum of squares = 0.0021
```

```
fit2
```

```
## variofit: model parameters estimated by OLS (ordinary least squares):
## covariance model is: exponential
## parameter estimates:
##   tausq sigmasq     phi
##  0.0675  0.2077 59.9998
## Practical Range with cor=0.05 for asymptotic range: 179.7434
##
## variofit: minimised sum of squares = 0.0056
```

```r
ph_geo=as.geodata(ph_df,coords.col=c(2,1),data.col=3)
variogram_ph=variog(ph_geo,uvec = seq(0,120,l=10),messages = FALSE)
fit3=variofit(variogram_ph,cov.model="sph",ini.cov.pars=c(0.23,100),
             fix.nugget=FALSE,nugget=0,weights='npairs',messages=FALSE)
fit4=variofit(variogram_ph,cov.model="exponential",ini.cov.pars=c(0.23,60),
             fix.nugget=FALSE,nugget=0,weights='npairs',messages=FALSE)
fit3
```

```
## variofit: model parameters estimated by WLS (weighted least squares):
## covariance model is: spherical
## parameter estimates:
##   tausq sigmasq     phi
##  0.0615  0.1622 65.9554
## Practical Range with cor=0.05 for asymptotic range: 65.95537
##
## variofit: minimised weighted sum of squares = 0.4801
```

```r
fit4
```

```
## variofit: model parameters estimated by WLS (weighted least squares):
## covariance model is: exponential
## parameter estimates:
##   tausq sigmasq     phi
##  0.0279  0.2049 25.1745
## Practical Range with cor=0.05 for asymptotic range: 75.4161
##
## variofit: minimised weighted sum of squares = 0.607
```

```r
# modelo sem efeito pepita
ph_geo=as.geodata(ph_df,coords.col=c(1,2),data.col=3)
variogram_ph=variog(ph_geo,uvec = seq(0,120,l=10),messages = FALSE)
fit31=variofit(variogram_ph,cov.model="sph",ini.cov.pars=c(0.23,100),
             fix.nugget=TRUE,nugget=0,weights='npairs',messages=FALSE)
fit41=variofit(variogram_ph,cov.model="exponential",ini.cov.pars=c(0.23,60),
             fix.nugget=TRUE,nugget=0,weights='npairs',messages=FALSE)
fit31
```

```
## variofit: model parameters estimated by WLS (weighted least squares):
## covariance model is: spherical
## fixed value for tausq =  0
## parameter estimates:
## sigmasq     phi
##  0.2215 54.5730
## Practical Range with cor=0.05 for asymptotic range: 54.57299
##
## variofit: minimised weighted sum of squares = 0.9122
```

```r
fit41
```

```
## variofit: model parameters estimated by WLS (weighted least squares):
## covariance model is: exponential
## fixed value for tausq =  0
## parameter estimates:
## sigmasq     phi
##  0.2295 21.7987
## Practical Range with cor=0.05 for asymptotic range: 65.30313
##
## variofit: minimised weighted sum of squares = 0.6449
```

```r
ph_geo=as.geodata(ph_df,coords.col=c(2,1),data.col=3)
variogram_ph=variog(ph_geo,uvec = seq(0,120,l=10),messages = FALSE)
fit5=variofit(variogram_ph,cov.model="sph",ini.cov.pars=c(0.23,60),
             fix.nugget=FALSE,nugget=0.01,weights='cressie',messages=FALSE)
fit6=variofit(variogram_ph,cov.model="exponential",ini.cov.pars=c(0.23,60),
             fix.nugget=FALSE,nugget=0.01,weights='cressie',messages=FALSE)
fit5
```

```
## variofit: model parameters estimated by WLS (weighted least squares):
## covariance model is: spherical
## parameter estimates:
##   tausq sigmasq     phi
##   0.052   0.170  60.000
## Practical Range with cor=0.05 for asymptotic range: 59.99996
##
## variofit: minimised weighted sum of squares = 14.7584
```

```r
fit6
```

```
## variofit: model parameters estimated by WLS (weighted least squares):
## covariance model is: exponential
## parameter estimates:
##   tausq sigmasq     phi
##  0.0352  0.2015 27.0918
## Practical Range with cor=0.05 for asymptotic range: 81.15985
##
## variofit: minimised weighted sum of squares = 13.1579
```

```r
var_fit=list(fit1,fit2,fit3,fit4,fit5,fit6)
plot(variogram_ph)
for(i in 1:6){
  lines(var_fit[[i]],lty=i,col=i, lwd=2)
}
legend('topleft',legend = c('Esferico MQO','Exp MQO', 'Esf MQP',
                            'Exp MQP','Esf cressie','Exp cressie'), lty=1:6,col=1:6)
```

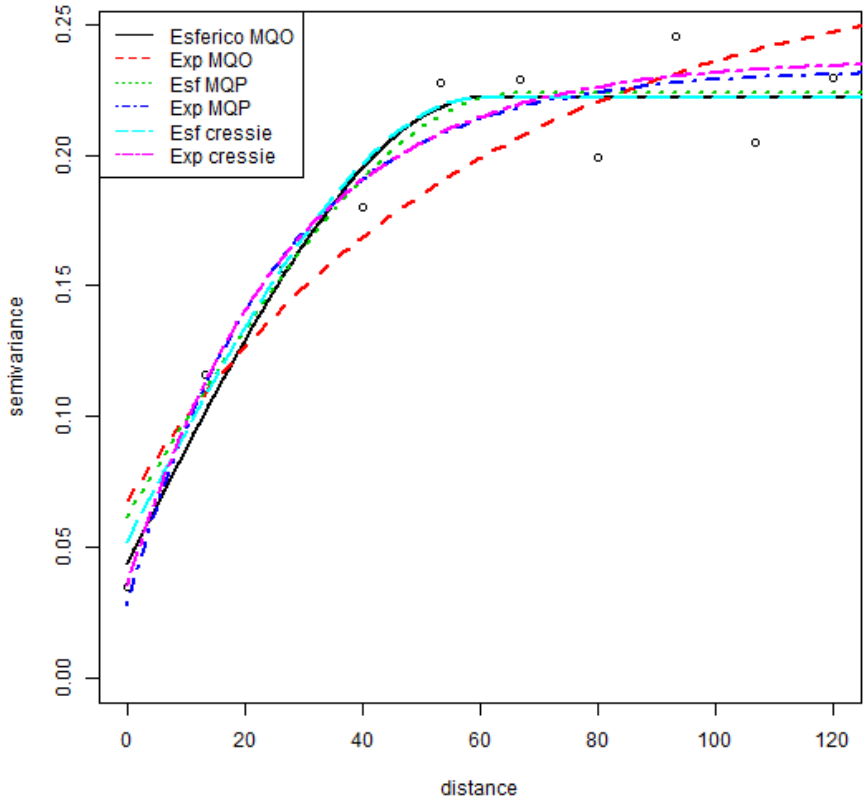

$\rightarrow$ As estimativas do semivariograma, isto é $\hat{\gamma}(\boldsymbol{h})$, estão correlacionadas e têm variâncias diferentes.

$\rightarrow$ MQO pressupões que as observaçoes sejam independentes com variância constante.

$\rightarrow$ Como alternativa, pode-se usar o método dos mínimos quadrados ponderados.

$\rightarrow$ Uma outra alternativa é o método dos mínimos quadrados generalizados (MQG).

Anisotropia

→ Os modelos de semivariograma vistos até aqui são para fenómenos isotrópicos, isto é, que dependem apenas da separação (distância) entre as obseravações.

→ Na prática, maior parte dos processos geoespaciais é de natureza anisotrópica, o que quer dizer que para além da distância, dependente também da direcção.

→ A anisotropia pode ser identificada com base no semivariograma experimental, calculado para várias direcções.

Anisotropia geométrica- Ocorre quando a amplitude varia consoante a direcção mas a soleira matem-se constante.

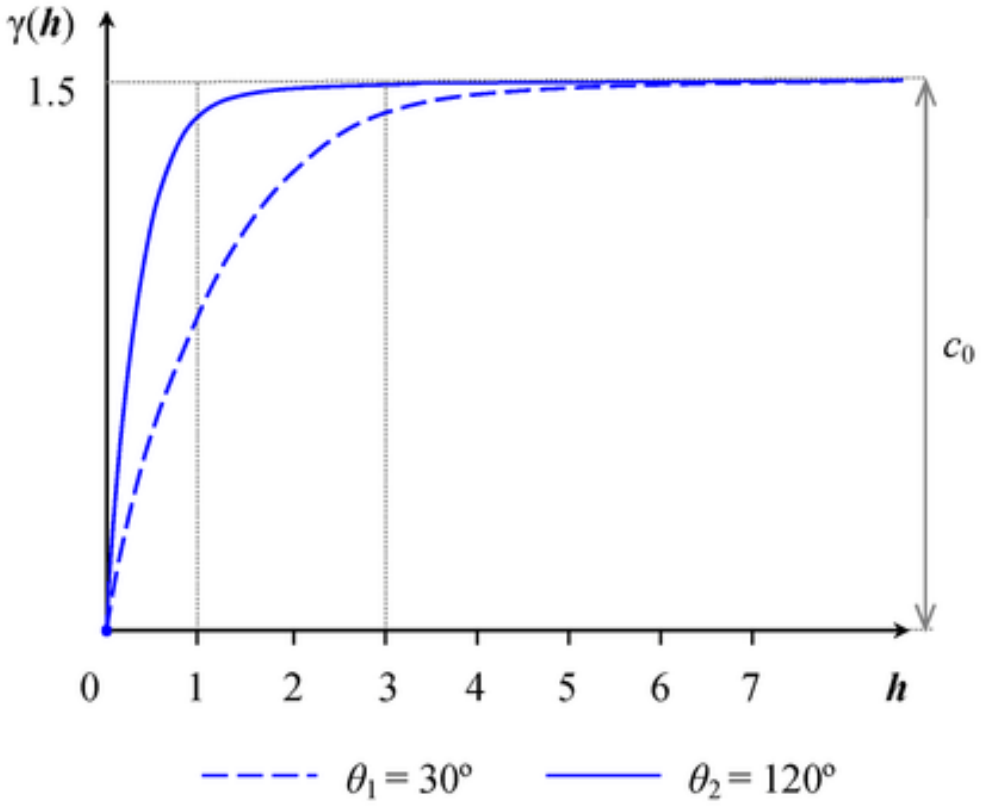

Correcção da anisotropia

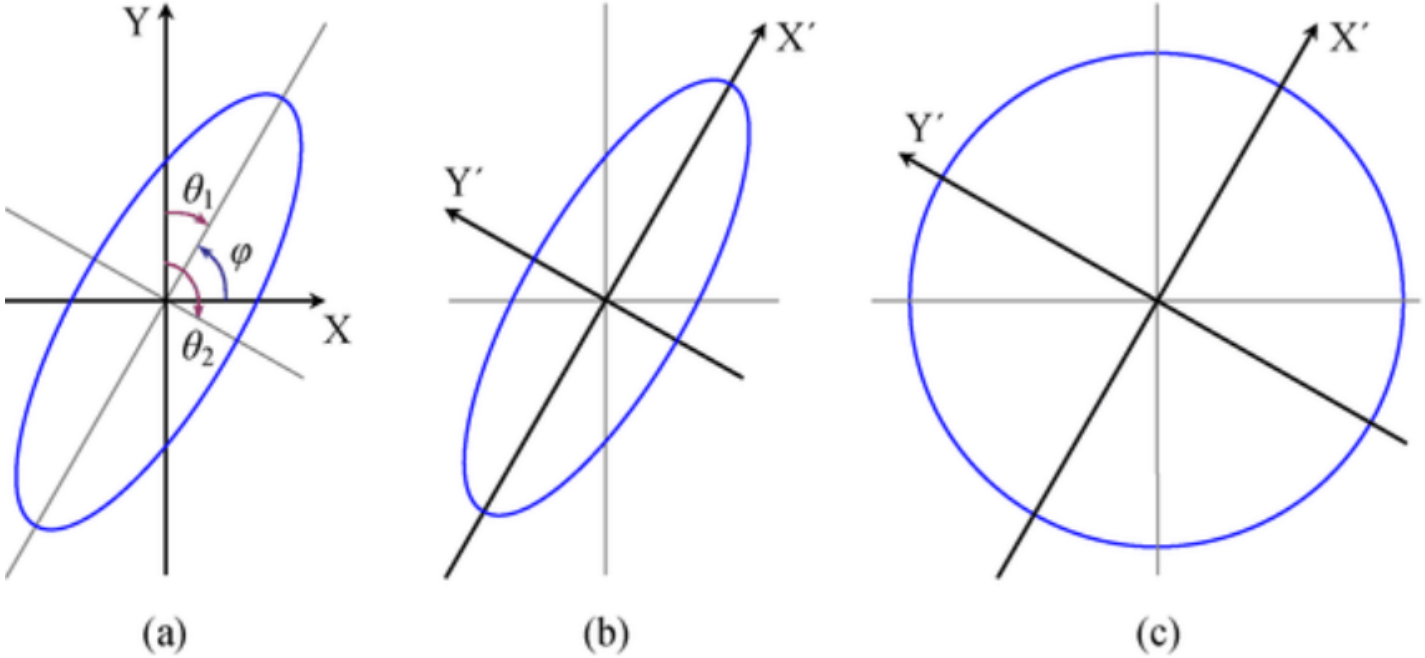

Converter a anisotropia geométrica em um processo isotrópico

Para o caso, em que, os eixos da elipse não coincidem com os eixos do sistema cartesiano ortogonal, antes de calcular as distâncias transformadas, é preciso aplicar a rotação dos eixos, de tal maneira que estes coincidam.

$$\begin{pmatrix} \Delta x' \\ \Delta y' \end{pmatrix} = \begin{pmatrix} \cos\phi & \sin\phi \\ -\sin\phi/R & \cos\phi/R \end{pmatrix} \begin{pmatrix} \Delta x \\ \Delta y \end{pmatrix} \tag{1}$$

,

onde $R = a_{min}/a_{max}$, $\Delta x = x_2 - x_1$ e $\Delta y = y_2 - y - 1$ e $\phi = 90° - \theta_1$. As novas distâncias serão calculadas usando a fórmula:

$$||\boldsymbol{h}'|| = \sqrt{(\Delta x')^2 + (\Delta y')^2}$$

Os valores do semivariograma teórico são calculados com base nas distâncias isotropadas.

$\rightarrow$ A fórmula apresentada no slide anterior é generalista. Todavia, para o caso onde as eixos da elipse coincidem com os eixos do sistema cartesiano ortogonal, as distâncias isotropadas podem ser calculados com base na seguinte fórmula:

$$||\boldsymbol{h}'|| = \sqrt{(\Delta x/a_x)^2 + (\Delta y/a_y)^2}$$

$\rightarrow$ A amplitude do semivariograma nas várias direcções terá uma amplitude igual a 1.

$\rightarrow$ Se optarmos por transformar a anisotropia num semivariograma de referência (por exemplo, o de maior amplitude em vez do semivariograma com amplitude igual a 1), então a distância $\boldsymbol{h}$ "isotropizada" fica igual a :

$$||\boldsymbol{h}'|| = \sqrt{\Delta x \left(a_x/a_x\right)^2 + \Delta y \left(a_x/a_y\right)^2}$$

onde a_x é a amplitude se semivariograma de referência e $r_x = a_x/a_x$, $r_y = a_x/a_y$, são os factores de anisotropia nos 2 eixos principais.

Exemplo- pH do Smoky Mountain

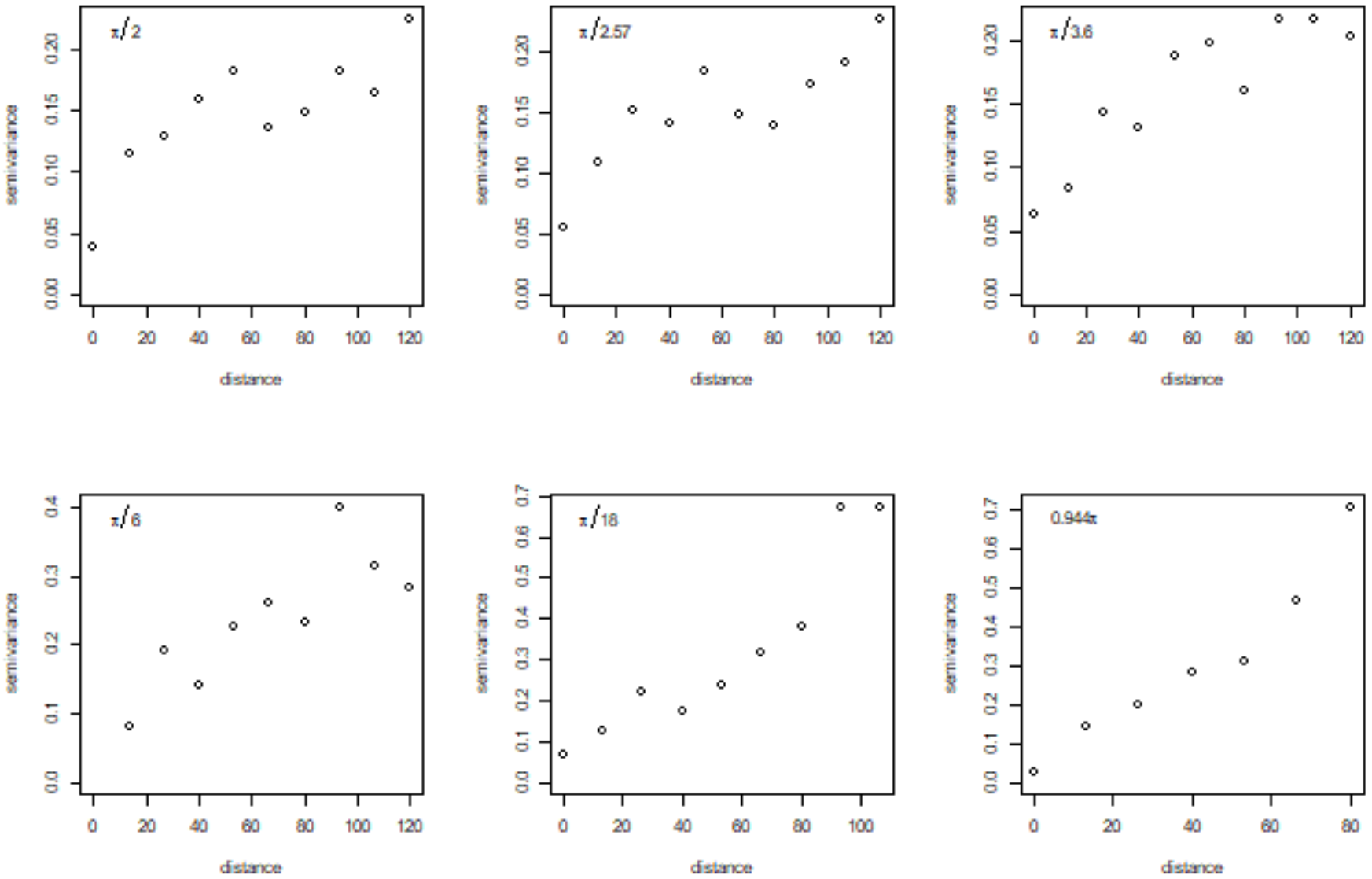

```r
var1=variog(ph_geo,uvec = seq(0,120,l=10),messages = FALSE, direction=pi/2)
var2=variog(ph_geo,uvec = seq(0,120,l=10),messages = FALSE, direction=pi/2.57)
var3=variog(ph_geo,uvec = seq(0,120,l=10),messages = FALSE, direction=pi/3.6)
var4=variog(ph_geo,uvec = seq(0,120,l=10),messages = FALSE, direction=pi/6)
var5=variog(ph_geo,uvec = seq(0,120,l=10),messages = FALSE, direction=pi/18)
var6=variog(ph_geo,uvec = seq(0,120,l=10),messages = FALSE, direction=0.944*pi)

fit1=variofit(var1,cov.model="exponential",ini.cov.pars=c(0.23,60),
              fix.nugget=FALSE,nugget=0.02,weights='npairs',messages=FALSE)
fit2=variofit(var2,cov.model="exponential",ini.cov.pars=c(0.23,60),
              fix.nugget=FALSE,nugget=0.02,weights='npairs',messages=FALSE)
fit3=variofit(var3,cov.model="exponential",ini.cov.pars=c(0.23,60),
              fix.nugget=FALSE,nugget=0.02,weights='npairs',messages=FALSE)
fit4=variofit(var4,cov.model="exponential",ini.cov.pars=c(0.23,60),
              fix.nugget=FALSE,nugget=0.02,weights='npairs',messages=FALSE)
fit5=variofit(var5,cov.model="exponential",ini.cov.pars=c(0.23,60),
              fix.nugget=FALSE,nugget=0.02,weights='npairs',messages=FALSE)
fit6=variofit(var6,cov.model="exponential",ini.cov.pars=c(0.23,60),
              fix.nugget=FALSE,nugget=0.02,weights='npairs',messages=FALSE)
fit1; fit2
```

```
## variofit: model parameters estimated by WLS (weighted least squares):
## covariance model is: exponential
## parameter estimates:
##       tausq     sigmasq         phi
##      0.0436    725.8673 139439.7379
## Practical Range with cor=0.05 for asymptotic range: 417724.1
##
## variofit: minimised weighted sum of squares = 0.9011

## variofit: model parameters estimated by WLS (weighted least squares):
## covariance model is: exponential
## parameter estimates:
##      tausq    sigmasq        phi
##     0.0475   122.5758 31611.0551
## Practical Range with cor=0.05 for asymptotic range: 94698.26
```

```
fit3; fit4; fit5; fit6
```

```
## variofit: model parameters estimated by WLS (weighted least squares):
## covariance model is: exponential
## parameter estimates:
##   tausq sigmasq     phi
##  0.0300  0.2817 58.4009
## Practical Range with cor=0.05 for asymptotic range: 174.9536
##
## variofit: minimised weighted sum of squares = 1.1912

## variofit: model parameters estimated by WLS (weighted least squares):
## covariance model is: exponential
## parameter estimates:
##   tausq sigmasq     phi
##  0.0667  0.1424 60.0115
## Practical Range with cor=0.05 for asymptotic range: 179.7783
##
## variofit: minimised weighted sum of squares = 0.2707

## variofit: model parameters estimated by WLS (weighted least squares):
## covariance model is: exponential
## parameter estimates:
##   tausq sigmasq     phi
##  0.0854  0.0980 60.0260
## Practical Range with cor=0.05 for asymptotic range: 179.8217
##
## variofit: minimised weighted sum of squares = 0.6764

## variofit: model parameters estimated by WLS (weighted least squares):
## covariance model is: exponential
## parameter estimates:
##      tausq    sigmasq        phi
##     0.0921    16.7275 10045.3723
## Practical Range with cor=0.05 for asymptotic range: 30093.25
##
```

$\rightarrow$ Os semivariogramas experimentais apresentados na página 50 sugerem que o processo é anisotrópico;

$\rightarrow$ O modelo exponencial apresenta melhor ajuste na direcção $\pi/2$;

$\rightarrow$ Os semivariogramas experimentais nas direcções $\pi/6$, $\pi/18$ e 0.944π, apresentam uma tendência, isto é, a medida que a distância aumenta o semivariograma aumenta;

$\rightarrow$ Quando o processo apresenta uma tendência, antes de calcular o semivariograma é preciso remover a tendência;

$\rightarrow$ Sendo o processo anisotrópico, o ideal é ajustar um semivariograma anisotrópico;

Remoção da tendência (DRIFT)

→ A presença notável da têndencia faz com que o pressuposto da estacionariedade seja violado;

→ A tendência torna as estimativas do semivariograma viciadas. Consequentemente, pode afectar negativamente o exercício de interpolação espacial.

Como identificar??

→ A tendência pode ser identificada a partir do semivariograma experimental, através de um comportamento crescente acima da soleira.

$\rightarrow$ A forma funcional da tendência, geralmente, é desconheciada;

$\rightarrow$ Se a tendência for linear, ajusta-se um modelo linear as dados, e extrai-se os resíduos. Ex:

$$Z(x, y) = \beta_0 + \beta_1 x + \beta_2 y$$

$\rightarrow$ A tendência pode, tambem, ser identificada a partir do diagrama de dispersão;

Exemplo- remoção da tendência- Smoky Mountain

```
trend=lm(ph~easting+northing, data=ph_df)
summary(trend)
```

```
##
## Call:
## lm(formula = ph ~ easting + northing, data = ph_df)
##
## Residuals:
##      Min       1Q   Median       3Q      Max
## -1.03489 -0.23082 -0.05789  0.20716  1.16752
##
## Coefficients:
##              Estimate Std. Error t value Pr(>|t|)
## (Intercept)  7.138924   0.045898 155.539  < 2e-16 ***
## easting      0.009396   0.002217   4.239 6.57e-05 ***
## northing    -0.002858   0.001462  -1.954   0.0546 .
## ---
## Signif. codes:  0 '***' 0.001 '**' 0.01 '*' 0.05 '.' 0.1 ' ' 1
##
## Residual standard error: 0.3975 on 72 degrees of freedom
## Multiple R-squared:  0.2037, Adjusted R-squared:  0.1816
## F-statistic: 9.209 on 2 and 72 DF,  p-value: 0.0002746
```

```
res=trend$residuals
res_df=cbind(ph_df,res)
res_geo=as.geodata(res_df,coords.col=c(2,1),data.col=5)
```

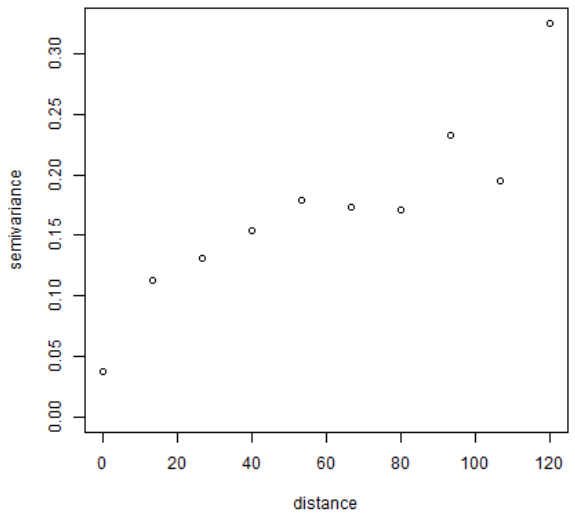


```
res_variog=variog(res_geo,uvec = seq(0,120,l=10),messages = FALSE, direction=0.944*pi)
res_fit=variofit(res_variog,cov.model="exponential",ini.cov.pars=c(0.23,60),
         fix.nugget=FALSE,nugget=0.02,weights='npairs',messages=FALSE)
res_fit
```

```
## variofit: model parameters estimated by WLS (weighted least squares):
## covariance model is: exponential
## parameter estimates:
##    tausq  sigmasq      phi
##   0.0906   0.4164 263.4559
## Practical Range with cor=0.05 for asymptotic range: 789.2432
##
## variofit: minimised weighted sum of squares = 0.2248
```

```r
var_trend=variog(ph_geo,uvec = seq(0,120,l=10),messages = FALSE, direction=0.944*pi,trend ="1st")
fit_trend=variofit(var_trend,cov.model="exponential",ini.cov.pars=c(0.23,60),
              fix.nugget=FALSE,nugget=0.02,weights='npairs',messages=FALSE)
fit_trend
```

```
## variofit: model parameters estimated by WLS (weighted least squares):
## covariance model is: exponential
## parameter estimates:
##    tausq  sigmasq      phi
##   0.0906   0.4164 263.4559
## Practical Range with cor=0.05 for asymptotic range: 789.2432
##
## variofit: minimised weighted sum of squares = 0.2248
```

```r
var_trend.quadra=variog(ph_geo,uvec = seq(0,120,l=10),messages = FALSE, direction=0.944*pi,trend ="2nd")
fit_trend.quadra=variofit(var_trend.quadra,cov.model="exponential",ini.cov.pars=c(0.23,60),
              fix.nugget=FALSE,nugget=0.02,weights='npairs',messages=FALSE)

fit_trend.quadra
```

```
## variofit: model parameters estimated by WLS (weighted least squares):
## covariance model is: exponential
## parameter estimates:
##   tausq sigmasq     phi
##  0.0958  0.0560 60.0282
## Practical Range with cor=0.05 for asymptotic range: 179.8283
##
## variofit: minimised weighted sum of squares = 0.4085
```

Anisotropia zonal- ocorre quando, para várias direcções a soleira é diferente. Geralmente, este tipo de anisotropia é difícil de encontrar na prática. O que tem acontecido, é encontrar uma combição da anisotropia geométrica e zonal.

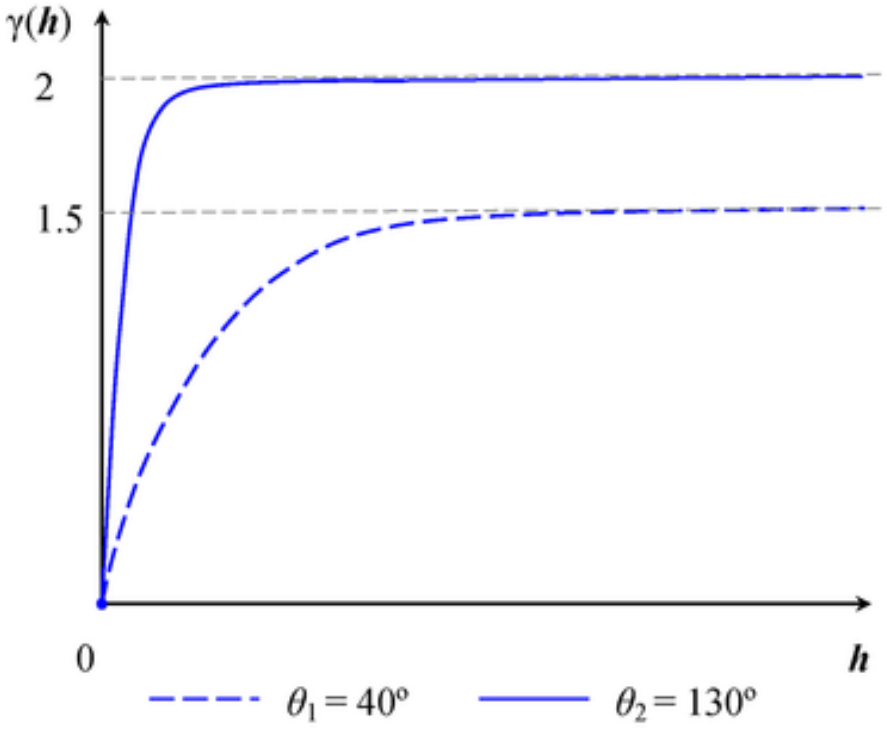

Interpolação espacial

→ Estimar valores em locais não amostrados usando observações vizinhas;

→ Assume-se que o atributo de interesse é contínuo em todo domínio;

→ Assume-se que o atributo é espacialmente dependente, com maior similaridade para dados mais próximos, e maior dissimilaridade para dados mais afastados;

Pode-se destacar dois tipos de interpolção: determínistica e estatística.

Interpolação inversa da distância ponderada (IVD)

→ A IVD é simplismente a média ponderada das observações vizinhas;

→ A interpolação de um ponto não amostrado pode ser calculada usando:

$$Z(\boldsymbol{s}_0) = \sum_{i=1}^{n} \lambda_i Z(\boldsymbol{s}_i)$$

λ_i representa o peso atribuído observação amostrada. O λ_i depende da distância entre o valor amostrado e o ponto a ser estimado, e é dado por:

$$\lambda_i = \frac{d_{0,i}^{-p}}{\sum_i^n d_{0,i}^{-p}}$$

$d_{0,i}$ representa a distância entre o ponto $\boldsymbol{s}_0$ e $\boldsymbol{s}_i$

$\rightarrow$ A soma dos pesos deve ser igual a 1, isto é, $\sum_i^n \lambda_i$;

$\rightarrow$ Geralmente, para p usa-se valores entre 1 e 3;

$\rightarrow$ $p = 2$ dá origem à inverso do quadrado da distância;

$\rightarrow$ Assumir $p = 0$ é mesmo que usar a média aritmética para estimar o valor de $Z(\boldsymbol{s}_0)$;

$\rightarrow$ A medida que o p aumenta, os pesos vão diminuindo em função da distância;

Exemplo-IVD

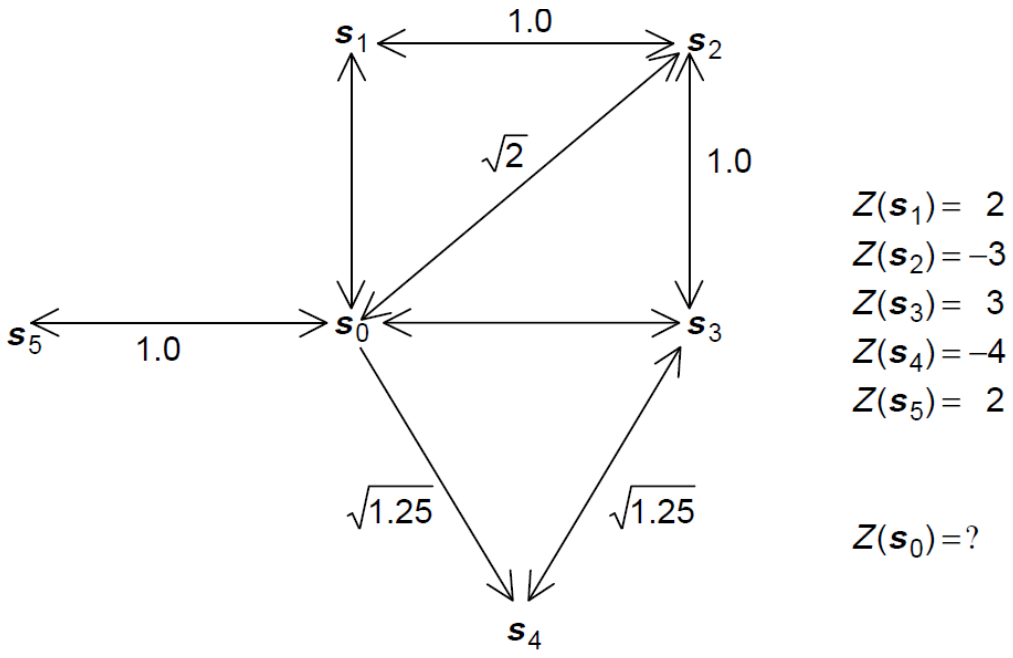

$\rightarrow$ Uma estimativa razoável para $\boldsymbol{s}_0$ é a média aritmética;

$\rightarrow$ Usando IVD as os valores em $\boldsymbol{s}_2$ e $\boldsymbol{s}_4$ terão menor; contribuição.

$\rightarrow$ Considerando $p = 2$, tem-se que $Z(\boldsymbol{s}_0) = 0.53$;

Exemplo-Ilustração em R

```
library(sp)
library(gstat)
# valores amostrados
X = c(61,63,64,68,71,73,75)
Y = c(139,140,129,128,140,141,128)
Z = c(477,696,227,646,606,791,783)
# locais não amostrados. Qual é o valor de Z1
X1 = 65; Y1 = 137

obser_dt = data.frame(X,Y,Z)
coordinates(obser_dt)= ~ X + Y
nao_obser_dt = data.frame(X1,Y1)
coordinates(nao_obser_dt)=~ X1 + Y1
idwmodel = idw(Z ~1, obser_dt,nao_obser_dt,
                    maxdist = Inf, idp = 2)
```

```
## [inverse distance weighted interpolation]
```

```
predZ= idwmodel@data$var1.pred
predZ
```

```
## [1] 597.6204
```

Este exemplo foi extraído em https://rpubs.com/hungle510/202761

Exemplo- IVD para interpolação do HIV

```
path='C:/Users/lucp8943/Dropbox/Geostatistics Class Material/Lecture notes'
hiv.df_prop=read.csv(paste(path, 'hiv_prev.csv', sep='/'), header=TRUE); head(hiv.df_prop)
shp1<-readOGR("MZGE52FL.shp")
shp<-readOGR("MOZ-level_1.shp")
# create outer boundary
shp2 <- gUnaryUnion(shp)
plot(shp)
plot(shp2, add=T, border = 'red')

# create coordinates of outer boundary
extractCoords <- function(sp.df)
{
  results <- list()
  for(i in 1:length(sp.df@polygons[[1]]@Polygons))
  {
    results[[i]] <- sp.df@polygons[[1]]@Polygons[[i]]@coords
  }
  results <- Reduce(rbind, results)
  results
}
coord<-extractCoords(shp2)

# make grid within area
plot.x = seq(30.21786,40.84447,0.1)
plot.y = seq(-26.86867,-10.47188,0.1)
x.pred = expand.grid(plot.x, plot.y)[,1]
y.pred = expand.grid(plot.x, plot.y)[,2]
pred.loc = data.frame(cbind(x.pred,y.pred))
pred.loc2<-SpatialPoints(pred.loc)
point.in.polygon = over(pred.loc2,shp2)
plot(shp2)
points(pred.loc2[!is.na(point.in.polygon),],cex=0.2)
coordinates(hiv.df_prop)= ~ long +lat
coordinates(pred.loc)=~x.pred+y.pred
```

Exemplo- IVD para interpolação do HIV (Cont.)

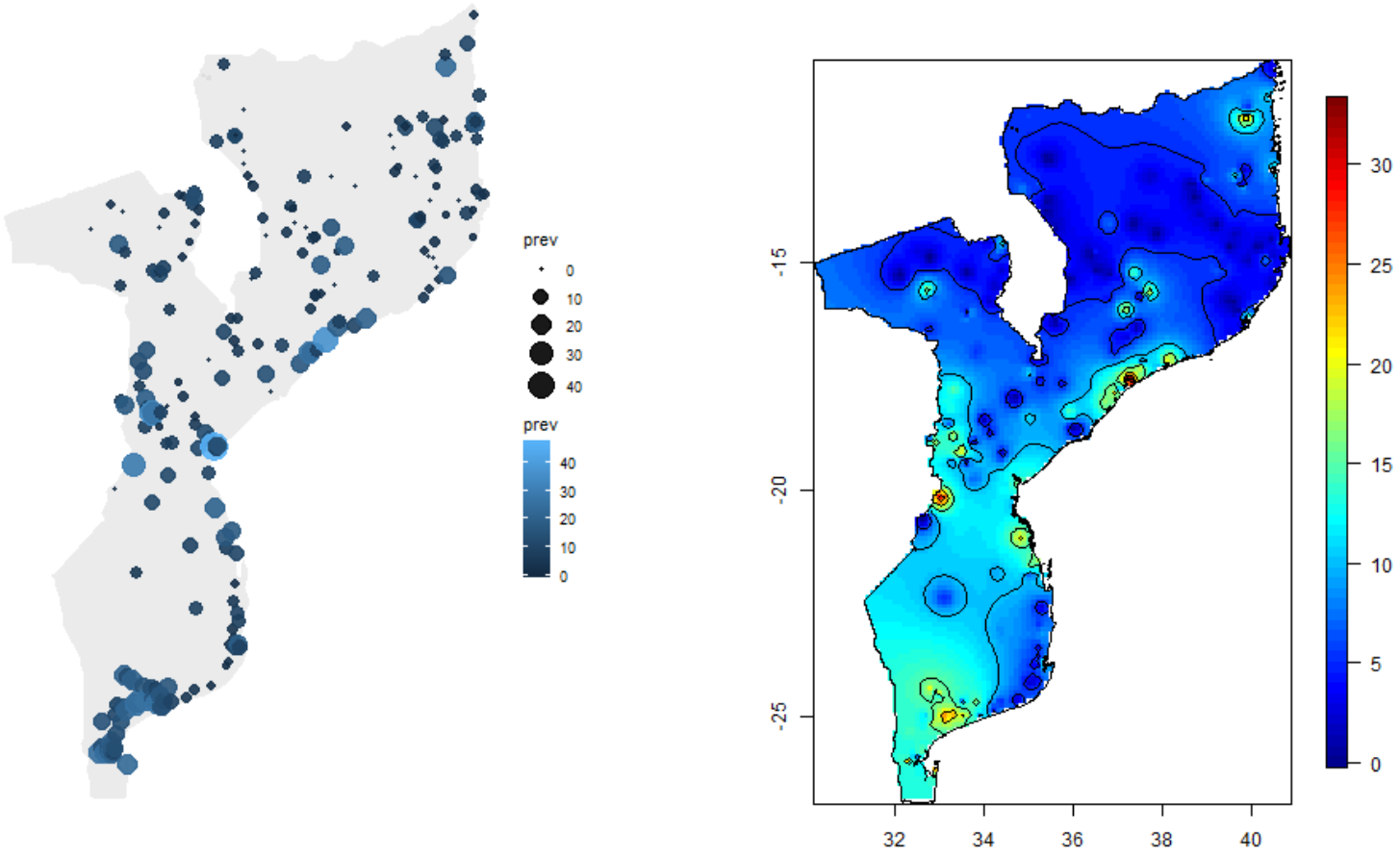

Figure 6: Do lado esquerdo temos valores observados e do lado direito temos valores previsto para todo o domínio

Interpolação por Krigagem

→ Krigagem- Técnica geoestatística para interpolação espacial;

→ Igual ao IVD, a Krigagem usa valores vizinhos para prever locais não amostrados ou estimar a média sobre um determinado bloco;

$$Z(\boldsymbol{s}_0) = \sum_{i=1}^{n} \lambda_i Z(\boldsymbol{s}_i)$$

→ A Krigagem é conhecida como um interpolador exacto;

Salientar que, a qualidade da interpolação depende de vários factores, nomeadamente:

i) tamanho da amostra e a qualidade dos dados;
ii) localização das observações (uniforme ou agrupados);
iii) distância entre os pontos observados e o ponto a ser previsto;
iv) continuidade espacial da variável aleatória;

Os métodos de Krigagem levam uma vantagem sobre os outros métodos de interpolação, pois para além de considerar a característica geométrica do processo, consideram também a estrutura espacial do fenómeno.

Noção de vizinhança

Krigagem usa valores circunvizinhos para estimação/previsão de uma local não amostrado.

1. Todos valores amostrados são incluídos na interpolação;
   - O impacto das observações distantes é insiginificante;
   - Inclusão de todas observções exige que o processo sejá estacionário em todo o domínio;
2. Apenas os pontos mais próximos do local a ser interpolado é que são considerados;
   - Apenas exige-se que o processo seja estacionário de segunda ordem ou quase intrínsecamente estacionário;

Não existe uma regra clara para definir a dimensão da vizinhança, contudo Webster & Oliver (2001) sugerem algumas directrizes:

1. Se os dados forem densos e o semivariograma tiver efeito pepita menor, então o raio da vizinhança pode ser igual a amplitude ou amplitude prática;
2. Se os o efeito pepita for maior, observações distantes do ponto a ser previsto irão ter um impacto significativo na interpolação e por essa razão devem ser incluídos na vizinhança;
3. Por outra, pode-se definir a vizinhança em termos de número mínimo e máximo de observações próximos do ponto a ser interpolado. Geralmente recomenda-se um mínimmo de $n \approx 7$ e um máximo $n \approx 20$.

Krigagem ordinária

Considere-se que uma função aleatória seja estacionária de segunda ordem, então

$$E[Z(\boldsymbol{s})] = \mu$$

com covariância definida por:

$$E[Z(\boldsymbol{s})Z(\boldsymbol{s}+\boldsymbol{h})] - \mu^2$$

e variograma dado por

$$E\Big([Z(\boldsymbol{s}+\boldsymbol{h}) - Z(\boldsymbol{s})]^2\Big)$$

A interpolação por Krigagem é dada por

$$Z^*(\boldsymbol{s}_0) = \sum_{i=1}^{n} \lambda_i Z(\boldsymbol{s}_i)$$

A interpolação depende dos valores dos λ_i

1. Estimador não enviesado

$$E[Z^*(\boldsymbol{s}_0)] = \mu \sum_{i=1}^{n} \lambda_i = E[Z(\boldsymbol{s})]$$

2. Variância do erro de estimação (erro quadrático médio) deve ser mínima. O que significa minimizar $E\Big[(Z^*(\boldsymbol{s}_0) - Z(\boldsymbol{s}_0))^2\Big]$ sujeito a restrição $\sum_{i=1}^{n} \lambda_i = 1$

Usando o método dos multiplicadores de lagrange os pesos (λ_i) podem ser calculados usando a seguinte expressão:

$$\boldsymbol{\lambda} = \boldsymbol{\Gamma}^{-1}\boldsymbol{\gamma}_0,$$

onde

$$\boldsymbol{\lambda} = \begin{bmatrix} \lambda_1 \\ \lambda_2 \\ \vdots \\ \lambda_n \\ m \end{bmatrix}, \boldsymbol{\Gamma} = \begin{bmatrix} \gamma(\boldsymbol{s}_1 - \boldsymbol{s}_1) & \cdots & \gamma(\boldsymbol{s}_1 - \boldsymbol{s}_n) & 1 \\ \gamma(\boldsymbol{s}_2 - \boldsymbol{s}_1) & \cdots & \gamma(\boldsymbol{s}_2 - \boldsymbol{s}_n) & 1 \\ \vdots & \ddots & \vdots & \vdots \\ \gamma(\boldsymbol{s}_n - \boldsymbol{s}_1 & \ldots & \gamma(\boldsymbol{s}_n - \boldsymbol{s}_n) & 1 \\ 1 & \cdots & 1 & 0 \end{bmatrix}, \boldsymbol{\gamma}_0 = \begin{bmatrix} \gamma(\boldsymbol{s}_0 - \boldsymbol{s}_1) \\ \gamma(\boldsymbol{s}_0 - \boldsymbol{s}_2) \\ \vdots \\ \gamma(\boldsymbol{s}_0 - \boldsymbol{s}_n) \\ 1 \end{bmatrix}$$

A variância de estimativa resultante da Krigagem é dada por:

$$\sigma^2(\boldsymbol{s}_0) = \boldsymbol{\lambda}^T \boldsymbol{\gamma}_0 = \sum_{i=1}^{n} \lambda_i \gamma(\boldsymbol{s}_0 - \boldsymbol{s}_i) + m$$

Assumindo-se que o erro de previsão $Z^*(\boldsymbol{s}_0) - Z(\boldsymbol{s}_0)$ segue distribuição normal, então o intervalo de previsão a 95% será dado por:

$$(Z^*(\boldsymbol{s}_0 \pm 1.96\sigma(\boldsymbol{s}_0))$$

Exemplo - Krigagem ordinária (pontual)

$\rightarrow$ Considere exercício no slide 66.

$\rightarrow$ Considere, igualmente, um semivariograma esférico com $c_0 = 0$, $c_s = 1$ e $a = 1.5$

$$\begin{bmatrix} \lambda_1 \\ \lambda_2 \\ \lambda_3 \\ \lambda_4 \\ \lambda_5 \\ m \end{bmatrix} = \begin{bmatrix} 0 & 0.852 & 0.995 & 1.00 & 0.995 & 1 \\ 0.852 & 0 & 0.852 & 1.00 & 1.00 & 1 \\ 0.995 & 0.852 & 0 & 0.911 & 1.00 & 1 \\ 1.00 & 1.00 & 0.911 & 0 & 1.00 & 1 \\ 0.995 & 1.00 & 1.00 & 1.00 & 0 & 1 \\ 1 & 1 & 1 & 1 & 1 & 0 \end{bmatrix}^{-1} \begin{bmatrix} 0.852 \\ 0.995 \\ 0.852 \\ 0.911 \\ 0.852 \\ 1 \end{bmatrix} = \begin{bmatrix} 0.256809 \\ 0.049996 \\ 0.241484 \\ 0.186251 \\ 0.265459 \\ 0.118743 \end{bmatrix}$$

$$Z^*(\boldsymbol{s}_0) = 0.257 \times 62 + 0.050 \times (-3) + 0.241 \times 3 + 0.186 \times (-4) + 0.265 \times 2 = 0.88$$

Exemplo- Dados de pH do Smoky Mountain

```
ph_geo=as.geodata(ph_df,coords.col=c(2,1),data.col=3)
variogram_ph=variog(ph_geo,uvec = seq(0,120,l=10),messages = FALSE)
fit3=variofit(variogram_ph,cov.model="sph",ini.cov.pars=c(0.23,100),
              fix.nugget=FALSE,nugget=0,weights='npairs',messages=FALSE)
x.range=as.integer(range(ph_df[,1]))
y.range=as.integer(range(ph_df[,2]))
grd=expand.grid(x=seq(from=x.range[1], to=x.range[2], length.out=50),
                      y=seq(from=y.range[1], to=y.range[2], length.out  =50))
kg_ph=krige.conv(ph_geo,locations = grd, krige = krige.control(obj.m = fit3))
```

```
## krige.conv: model with constant mean
## krige.conv: Kriging performed using global neighbourhood
```

```
kg_ph$predict
```

```
##    [1] 7.308242 7.286815 7.257535 7.223387 7.192816 7.167306 7.146242
##    [8] 7.126020 7.103787 7.080872 7.056975 7.031615 7.019327 7.007065
##   [15] 6.989325 6.968901 6.950733 6.942323 6.948501 6.976496 7.018352
##   [22] 7.066827 7.179687 7.291974 7.372481 7.422265 7.450354 7.467347
##   [29] 7.482102 7.498229 7.516474 7.536553 7.557614 7.578573 7.597988
##   [36] 7.615639 7.628826 7.636905 7.640956 7.639331 7.630393 7.619320
##   [43] 7.607137 7.594626 7.584877 7.576486 7.561943 7.537759 7.504155
##   [50] 7.467748 7.309336 7.287117 7.257313 7.222630 7.191364 7.165117
##   [57] 7.143185 7.121556 7.098915 7.075831 7.051864 7.028314 7.013050
##   [64] 6.999818 6.983992 6.966790 6.952468 6.945976 6.951796 6.974345
##   [71] 7.008500 7.058825 7.144774 7.236176 7.307538 7.355848 7.387020
##   [78] 7.409348 7.429696 7.451964 7.476419 7.502606 7.529284 7.555393
##   [85] 7.580196 7.601843 7.618469 7.630029 7.638311 7.639510 7.633150
##   [92] 7.623603 7.613173 7.602654 7.595528 7.589950 7.577693 7.555989
##   [99] 7.523764 7.486218 7.309814 7.286994 7.257229 7.222357 7.190180
##  [106] 7.163195 7.140387 7.118218 7.095798 7.073251 7.050310 7.028878
##  [113] 7.011938 6.997234 6.982175 6.967052 6.955654 6.950624 6.958060
##  [120] 6.979060 7.010043 7.056114 7.121813 7.192826 7.252086 7.295008
```

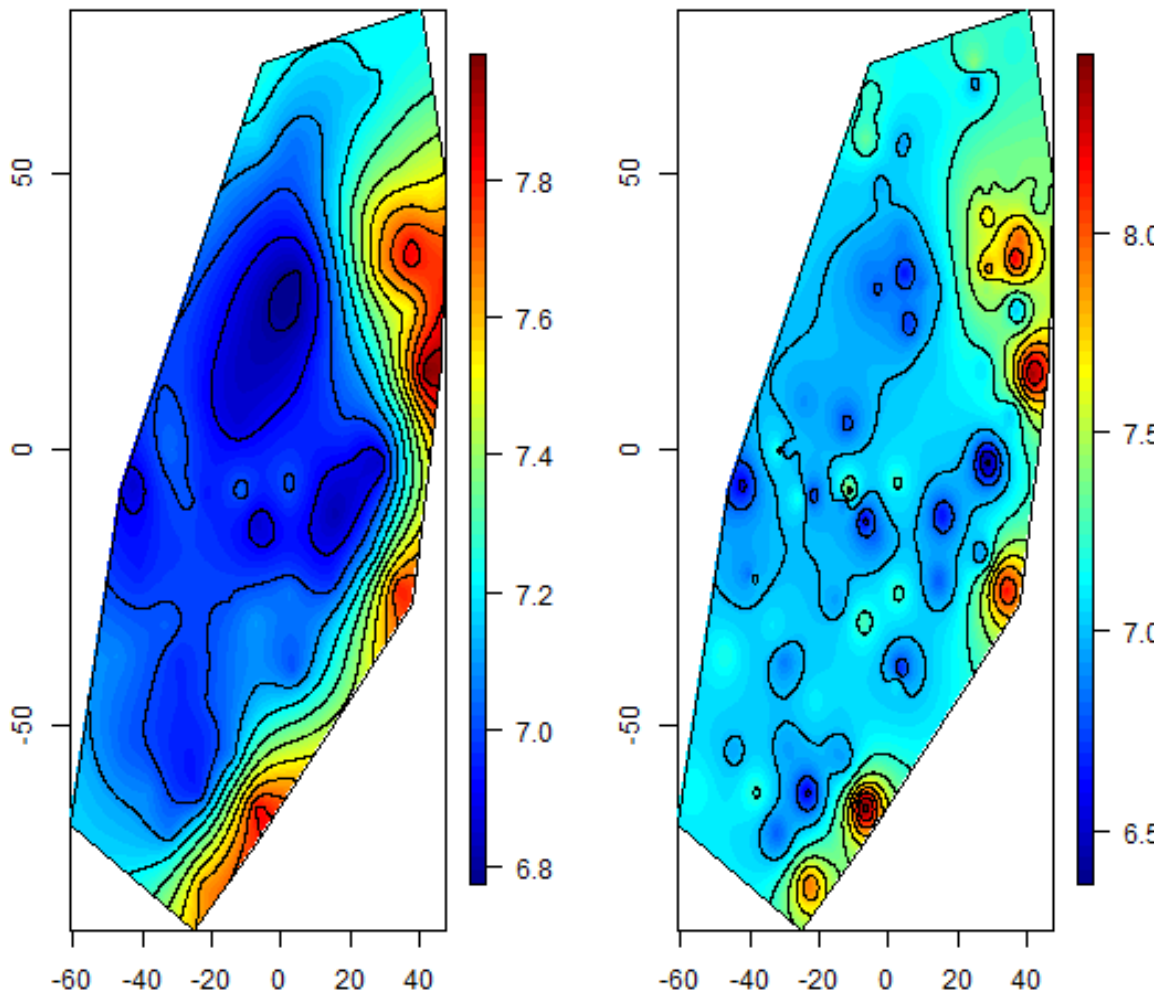

Figure 7: A figura mostra as interpolações, do lado esquerdo por Krigagem e do lado direito por Inverso da distância.

Durante o processo do estudo da continuidade espacial observou-se que, este processo apresenta um comportamento anisotrópico.

```
# Desenho da malha para efeitos de Krigagem
# esta malha contem os pontos que serão considerados
# como locais não amostrados , para os quais serão feitas
# as interpolações
plot.x = seq(-60.93033 , 47.48567,0.1)
plot.y = seq(-87.08972,79.58228,0.1)
x.pred = expand.grid(plot.x, plot.y)[,1]
y.pred = expand.grid(plot.x, plot.y)[,2]
pred.loc = data.frame(cbind(x.pred,y.pred))
pred.loc2<-SpatialPoints(pred.loc)
point.in.polygon = over(pred.loc2,sps)
plot(sps)
points(pred.loc2[!is.na(point.in.polygon),],cex=0.2)
plot.index = matrix(point.in.polygon, nrow=length(plot.x), ncol=length(plot.y))

# Krigagem com correcção  da anisotropia
kg_ph=krige.conv(ph_geo,locations = pred.loc,
                 krige = krige.control(cov.model ='exponential',nugget =0,
                                       cov.pars =c(0.2725,36.25),aniso.pars = c(7*pi/18,36.25/16.93) ))

pred.kg=kg_ph$predict

# visualização das intgerpolações por Krigagem
plot.mean.kg= matrix(pred.kg, nrow=length(plot.x), ncol=length(plot.y))
plot.mean.kg[is.na(plot.index)] = NA
image.plot(x=plot.x,y=plot.y,z=plot.mean.kg,xlab="",ylab="")
contour(x=plot.x,y=plot.y,z=plot.mean.kg,xlab="",ylab="",add=TRUE, drawlabels=FALSE)
plot(sps,add=T)
```

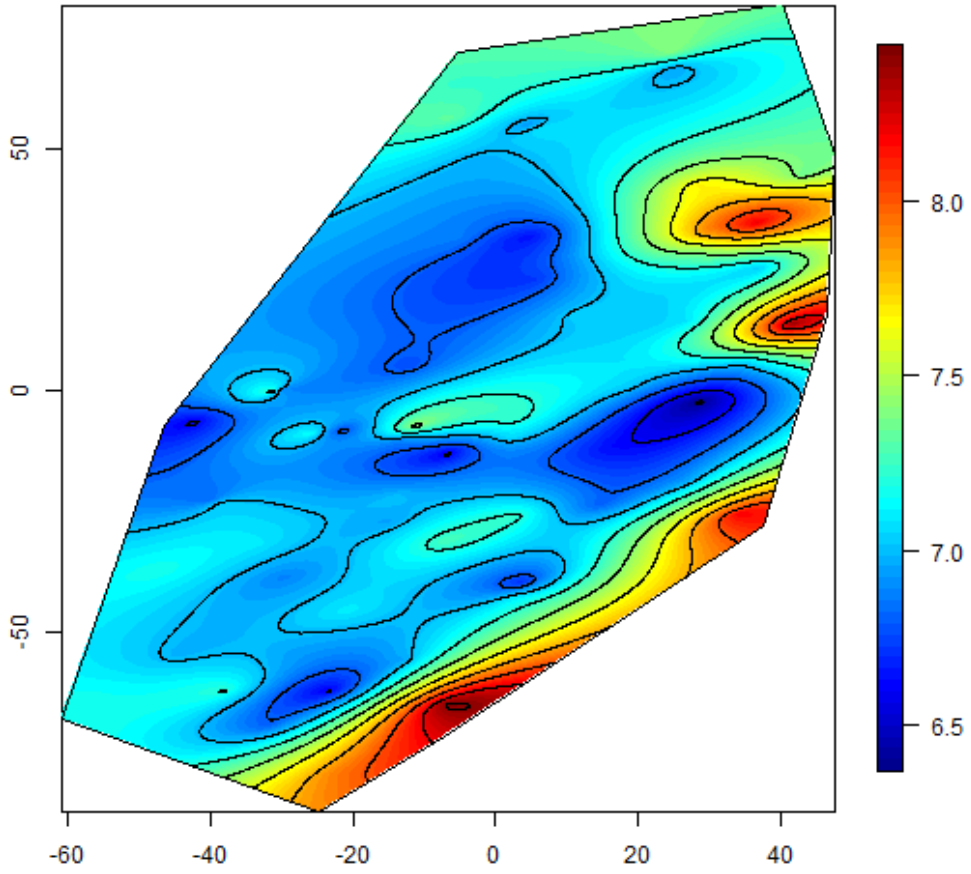

Figure 8: Distribuição espacial do pH. Valores interpolados com correcção da anisotropia geométrica

Krigagem Simples

$\rightarrow$ Este método não difere tanto da Krigagem Ordinária;

$\rightarrow$ Assume que a média do processo é conhecida;

$\rightarrow$ O processo de interpolação leva em consideração o conhecimento da média;

$$Z^*(\boldsymbol{s}_0) = \sum_{i=1}^{n} \lambda_i Z(\boldsymbol{s}_i) + (1 - \sum_{i=1}^{n} \lambda_i)\mu$$